INFORME TÉCNICO OFICIAL

CN
PARTIDA A10009201

El lote A10009201 en el Distrito CN presenta una paradoja crítica. Si bien permite una altura de 9 metros y un FOS del 0.75, la capacidad oficial de construcción es de 0 m². Esto significa que, a pesar de parámetros aparentemente favorables, el desarrollo de cualquier edificación está completamente impedido, lo que anula cualquier potencial constructivo. Una limitación severa e insalvable.

GEOMETRÍA DEL SUELO

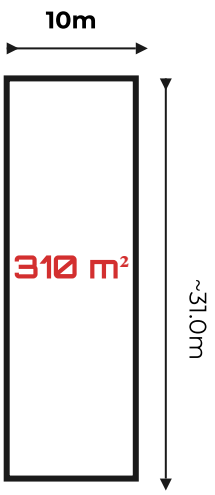

DISTRITO
CN

SUPERFICIE TOTAL
310 m²

FRENTE LOTE
10 m

INCIDENCIA ESTIMADA
Alta
MULTIPLICADOR DE SUELO

OCUPACIÓN (F.O.S.)

FOS: 0.75 - Permite ocupar 232.50 m² en PB.

CORTE ESQUEMÁTICO

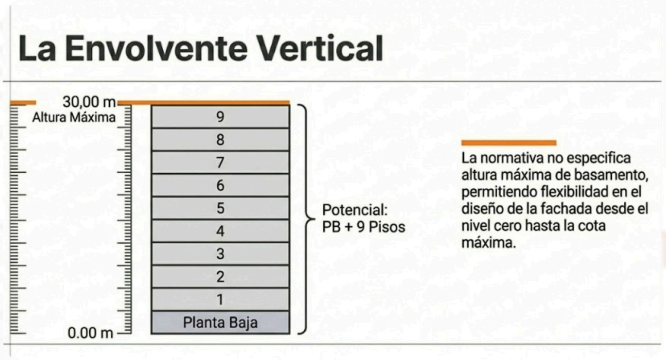

/// ANÁLISIS DE INTELIGENCIA ARTIFICIAL

El predio, con 10 metros de frente y 310 m² de superficie, se clasifica como 'Entre Medianeras'. Su ubicación en el Distrito CN, con un FOS del 0.75 y una altura permitida de 9 metros, sugeriría inicialmente un considerable potencial constructivo. Sin embargo, la sorprendente 'Superficie Máxima Construible (Oficial)' de 0 m² revela una restricción urbanística profunda. Esta anomalía indica la presencia de normativas específicas, como afectaciones por patrimonio, servidumbres, zonas inundables, o cláusulas de reordenamiento territorial que prevalecen sobre los indicadores básicos de FOS y altura. Aunque estos últimos daban pie a un volumen considerable, esta posibilidad queda completamente anulada por la directriz oficial, impidiendo cualquier desarrollo y generando una inviabilidad constructiva.

POTENCIAL CONSTRUCTIVO

PB + 3 PISOS ALTOS (9m)

PERSPECTIVA OBJETIVO

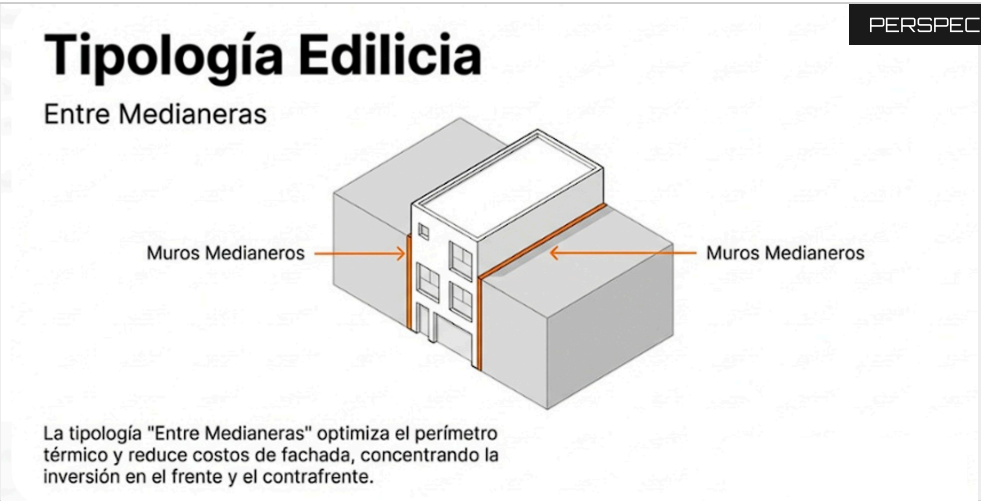

TABLA DE VALUACIÓN PRELIMINAR

INDICADOR	VALOR ESTIMADO
Sup. Vendible Estimada (bruta)	**0 m²**
Costo Construcción	U$S 1.400 / m²
Ticket Venta Promedio	U$S 2.800 / m²
RENTABILIDAD BRUTA	**ALTO POTENCIAL**

DICTAMEN FINAL

Financieramente, la inviabilidad constructiva del lote A10009201 es total. Con una Superficie Máxima Construible de 0 m², el valor del terreno para fines de desarrollo inmobiliario es nulo o residual. Cualquier inversión potencial en este activo carecería de rentabilidad por construcción, transformándolo en una carga o un activo de valor muy bajo, limitado quizás a usos no edificables si fueran permitidos o como espacio verde. Su adquisición solo podría justificarse por un propietario colindante para ampliar un lote sin restricciones.