INFORME TÉCNICO OFICIAL
ADREMA: A11304091

GEOMETRÍA DEL SUELO

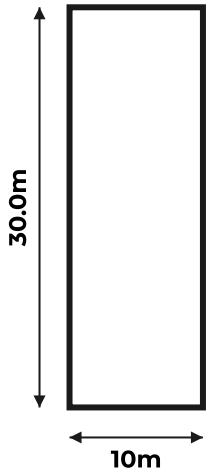

300 m²

DISTRITO
PE1UG2-AI1

SUPERFICIE TOTAL
300 m²

FRENTE LOTE
10 m

INCIDENCIA ESTIMADA

A DETERMINAR

MULTIPLICADOR DE SUELO

ENVOLVENTE VERTICAL NORMATIVA

OCUPACIÓN (F.O.S.)

FOS: 0.7
Representación de ocupación
en Planta Baja

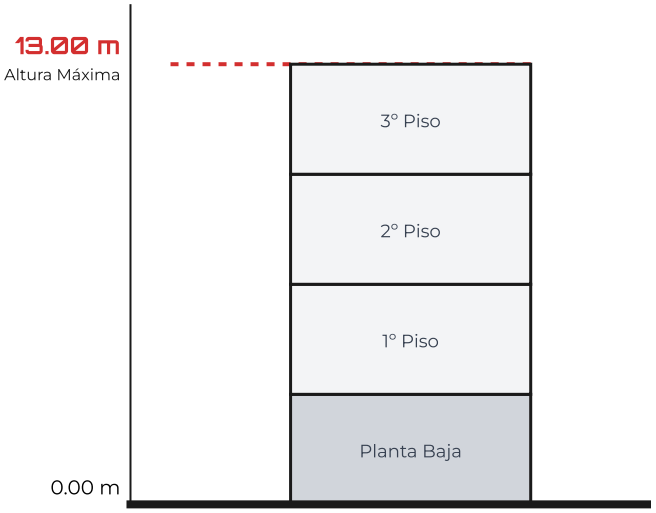

Potencial: PB + 3 Pisos

/// ANÁLISIS DE INTELIGENCIA ARTIFICIAL

El análisis detallado de inteligencia artificial se encuentra temporalmente no disponible debido a la alta demanda del servicio. Los datos normativos, gráficos de ocupación y volumetría presentados en este informe son precisos y surgen directamente de la normativa vigente.

POTENCIAL CONSTRUCTIVO

PB + 3 PISOS ALTOS (12m)

PERSPECTIVA

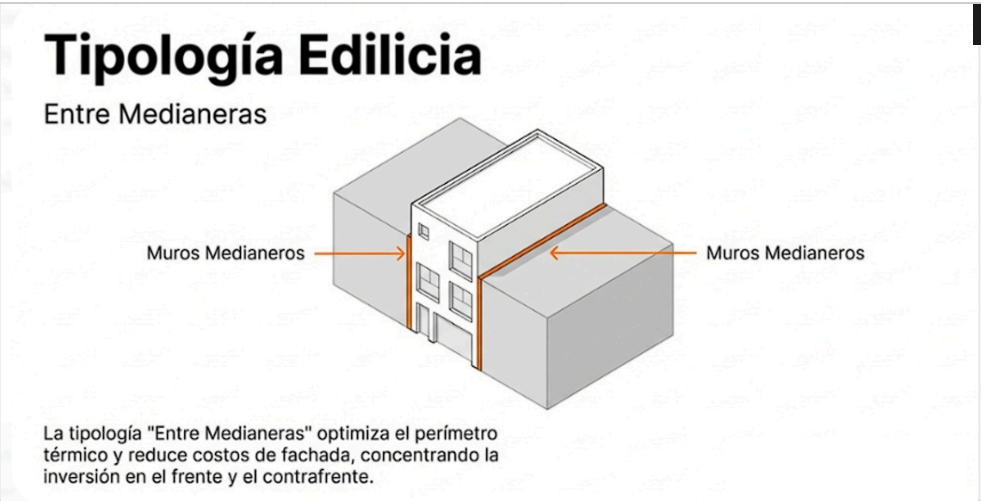

TABLA DE VALUACIÓN PRELIMINAR

INDICADOR	VALOR ESTIMADO
Sup. Vendible Estimada (bruta)	**672.00 m²**
Costo Construcción	U$S 1.400 / m²
Ticket Venta Promedio	U$S 2.800 / m²
RENTABILIDAD BRUTA	**ALTO POTENCIAL**

CONCLUSIÓN FINAL

La volumetría potencial se define por una huella de ocupación en planta baja de 210.00m² (300m² * 0.7 FOS). La altura máxima de 13m, con una estimación conservadora de 3m por nivel, permite la construcción de un edificio de 3 plantas (Planta Baja + 2 pisos tipo). Asumiendo una ocupación similar en las plantas superiores, la superficie bruta total estimada ascendería a 840.00m². Aplicando un factor de eficiencia del 80% para obtener la superficie vendible, se proyectan aproximadamente 672.00m² de superficie comercializable. El Distrito PE1UG2-AI1 Sup. Parcela: 300 m² Frente: 10 m sugiere una zona de desarrollo con potencial mixto. En términos de rentabilidad, con un costo de construcción promedio de U$S 1400/m² y venta de U$S 3000/m², el costo total ascendería a U$S 940.800 y los ingresos por venta a U$S 2.016.000. Esto arroja un margen bruto significativo de U$S 1.075.200 antes de impuestos e incidencia del terreno.