INFORME TÉCNICO OFICIAL
ADREMA: A10045711

GEOMETRÍA DEL SUELO

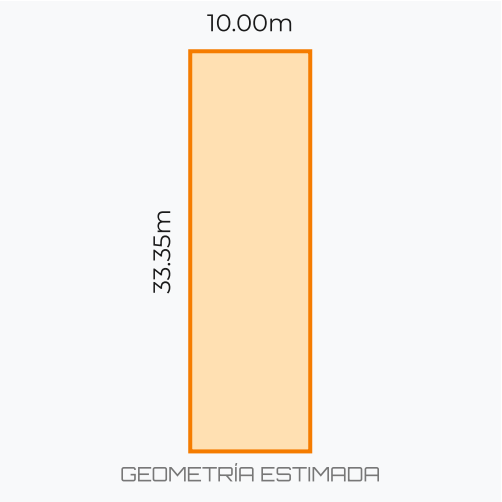

DISTRITO
CN

SUPERFICIE TOTAL
333.5 m²

FRENTE LOTE
10 m

INCIDENCIA ESTIMADA
Alta
MULTIPLICADOR DE SUELO

OCUPACIÓN (F.O.S.)

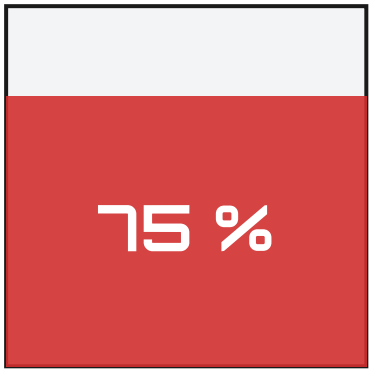

FOS: 0.75
Representación de ocupación
en Planta Baja

ENVOLVENTE VERTICAL NORMATIVA

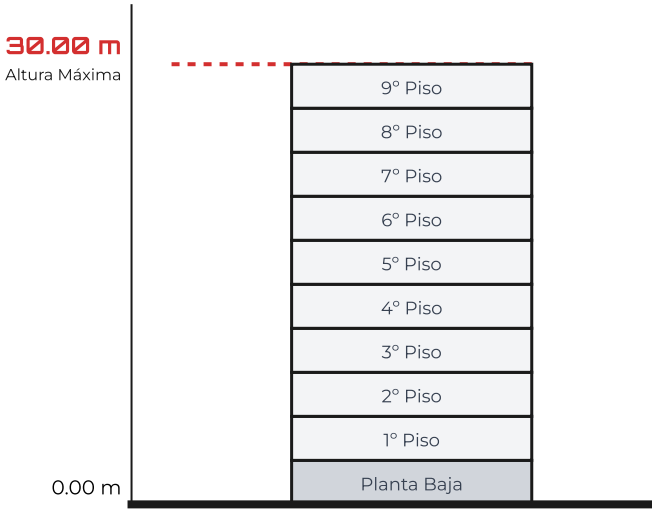

Potencial: PB + 9 Pisos

ANÁLISIS DE INTELIGENCIA ARTIFICIAL

La parcela de 333.5 m² con un FOS de 0.75 permite construir hasta 250.125 m² de superficie edificable, lo que representa un uso eficiente del espacio. La altura máxima de 30 m ofrece la posibilidad de múltiples niveles, ideal para usos mixtos. Su frente de 10 m sugiere un diseño que podría integrar una fachada atractiva y funcional, contribuyendo al urbanismo del distrito. Es fundamental considerar la integración con el entorno, asegurando que el nuevo desarrollo complemente la infraestructura existente y fomente la actividad comunitaria.

POTENCIAL CONSTRUCTIVO

PB + 9 PISOS ALTOS (30m)

TABLA DE VALUACIÓN PRELIMINAR

INDICADOR	VALOR ESTIMADO
Sup. Vendible Estimada (bruta)	**1814.40 m²**
Costo Construcción	U$S 1050 / m²
Ticket Venta Promedio	U$S 2100 / m²
RENTABILIDAD BRUTA	**ALTO POTENCIAL**

CONCLUSIÓN FINAL

La altura máxima de 30m, con una estimación conservadora de 3m por nivel, permite la construcción de un edificio de 10 plantas (Planta Baja + 9 pisos tipo). Asumiendo una ocupación similar en las plantas superiores, la superficie bruta total estimada ascendería a 2268.00 m². Aplicando un factor de eficiencia del 80% para obtener la superficie vendible, se proyectan aproximadamente 1814.40 m² de superficie comercializable. Un costo de construcción promedio de U$S 1050/m² (valor extraído de la planilla "TABLA DE VALUACIÓN PRELIMINAR") y venta de U$S 2100/m² (valor extraído de la planilla "TABLA DE VALUACIÓN PRELIMINAR"), el costo total ascendería a U$S 2.381.400 y los ingresos por venta a U$S 3.810.240. Esto arroja un margen bruto significativo de U$S 1.428.840.