INFORME TÉCNICO OFICIAL
ADREMA: A10065351

GEOMETRÍA DEL SUELO

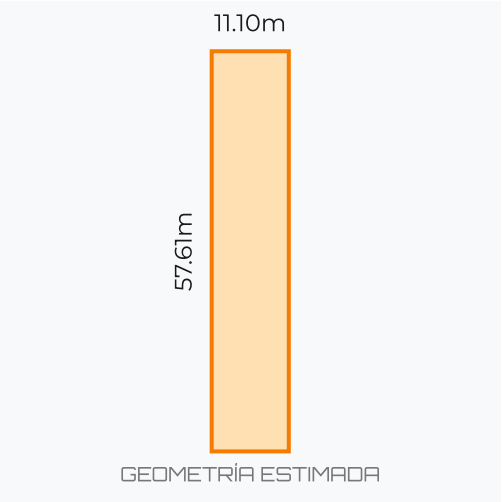

DISTRITO
CN

SUPERFICIE TOTAL
639.45 m²

FRENTE LOTE
11.1 m

INCIDENCIA ESTIMADA
Alta
MULTIPLICADOR DE SUELO

OCUPACIÓN (F.O.S.)

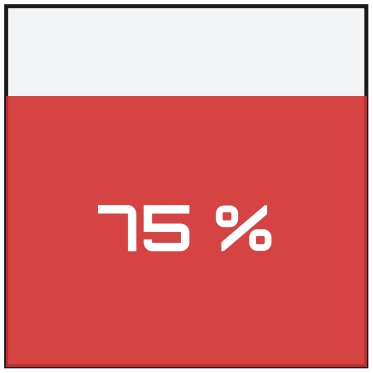

FOS: 0.75
Representación de ocupación
en Planta Baja

ENVOLVENTE VERTICAL NORMATIVA

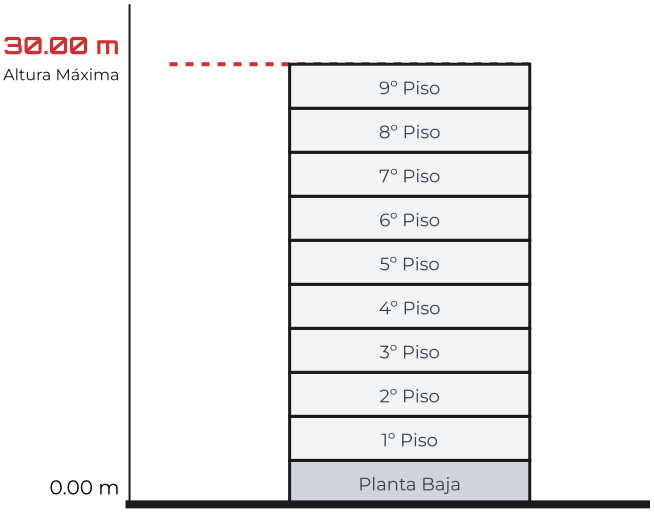

Potencial: PB + 9 Pisos

ANÁLISIS DE INTELIGENCIA ARTIFICIAL

La parcela de 639.45 m² ofrece una oportunidad valiosa para un desarrollo vertical, maximizando el FOS de 0.75. La altura permitida de 30 m sugiere un enfoque moderno en el diseño, permitiendo la creación de espacios habitables eficientes. La ubicación, junto a otros desarrollos, podría fomentar la cohesión comunitaria y mejorar la infraestructura urbana. Se recomienda considerar la integración de áreas verdes y espacios públicos para enriquecer la calidad de vida de los futuros residentes.

POTENCIAL CONSTRUCTIVO

PB + 9 PISOS ALTOS (30m)

TABLA DE VALUACIÓN PRELIMINAR

INDICADOR	VALOR ESTIMADO
Sup. Vendible Estimada (bruta)	**3478.40 m²**
Costo Construcción	U$S 1050 / m²
Ticket Venta Promedio	U$S 2100 / m²
RENTABILIDAD BRUTA	**ALTO POTENCIAL**

CONCLUSIÓN FINAL

La altura máxima de 30m, con una estimación conservadora de 3m por nivel, permite la construcción de un edificio de 10 plantas (Planta Baja + 9 pisos tipo). Asumiendo una ocupación similar en las plantas superiores, la superficie bruta total estimada ascendería a 4348.00 m². Aplicando un factor de eficiencia del 80% para obtener la superficie vendible, se proyectan aproximadamente 3478.40 m² de superficie comercializable. Un costo de construcción promedio de U$S 1050/m² (valor extraído de la planilla "TABLA DE VALUACIÓN PRELIMINAR") y venta de U$S 2100/m² (valor extraído de la planilla "TABLA DE VALUACIÓN PRELIMINAR"), el costo total ascendería a U$S 4.565.400 y los ingresos por venta a U$S 7.304.640. Esto arroja un margen bruto significativo de U$S 2.739.240.