INFORME TÉCNICO OFICIAL
ADREMA: A10169791

GEOMETRÍA DEL SUELO

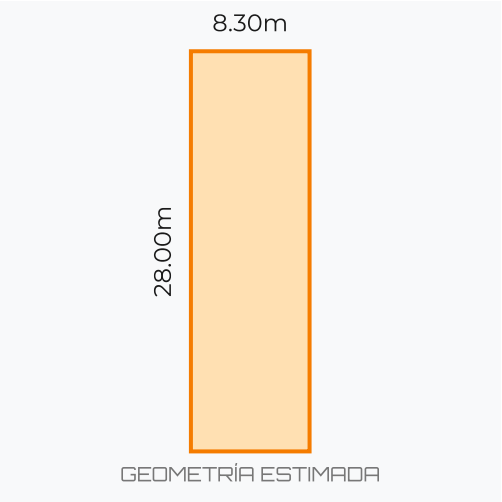

DISTRITO
CN

SUPERFICIE TOTAL
232.36 m²

FRENTE LOTE
8.3 m

INCIDENCIA ESTIMADA
Alta
MULTIPLICADOR DE SUELO

OCUPACIÓN (F.O.S.)

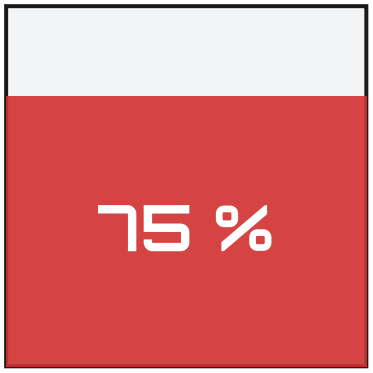

FOS: 0.75
Representación de ocupación
en Planta Baja

ENVOLVENTE VERTICAL NORMATIVA

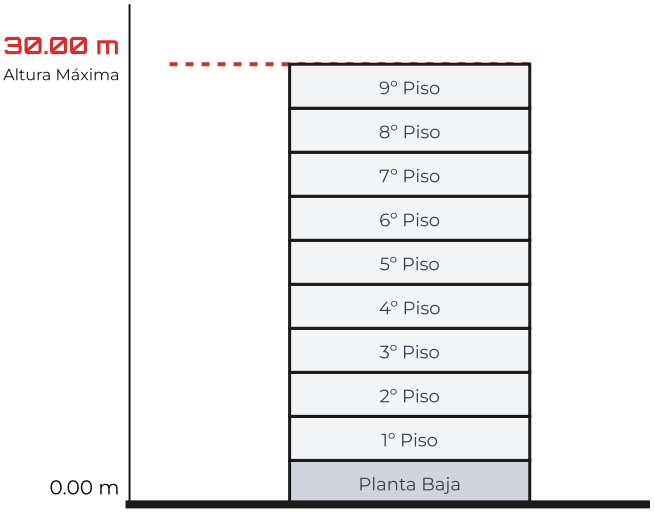

Potencial: PB + 9 Pisos

ANÁLISIS DE INTELIGENCIA ARTIFICIAL

La ubicación de la parcela en el Distrito CN, junto con su FOS de 0.75, sugiere un potencial considerable para edificación. La altura permitida de 30 m permite la incorporación de varios niveles, favoreciendo así la densificación urbana. Es crucial considerar las infraestructuras circundantes y el impacto en la movilidad. Además, la relación con el entorno y la integración de espacios verdes serán determinantes para un desarrollo sostenible y armónico con el tejido urbano existente.

POTENCIAL CONSTRUCTIVO

PB + 9 PISOS ALTOS (30m)

TABLA DE VALUACIÓN PRELIMINAR

INDICADOR	VALOR ESTIMADO
Sup. Vendible Estimada (bruta)	**1264.00 m²**
Costo Construcción	U$S 1050 / m²
Ticket Venta Promedio	U$S 2100 / m²
RENTABILIDAD BRUTA	**ALTO POTENCIAL**

CONCLUSIÓN FINAL

La altura máxima de 30m, con una estimación conservadora de 3m por nivel, permite la construcción de un edificio de 10 plantas (Planta Baja + 9 pisos tipo). Asumiendo una ocupación similar en las plantas superiores, la superficie bruta total estimada ascendería a 1580.00 m². Aplicando un factor de eficiencia del 80% para obtener la superficie vendible, se proyectan aproximadamente 1264.00 m² de superficie comercializable. Un costo de construcción promedio de U$S 1050/m² (valor extraído de la planilla "TABLA DE VALUACIÓN PRELIMINAR") y venta de U$S 2100/m² (valor extraído de la planilla "TABLA DE VALUACIÓN PRELIMINAR"), el costo total ascendería a U$S 1.659.000 y los ingresos por venta a U$S 2.654.400. Esto arroja un margen bruto significativo de U$S 995.400.