INFORME TÉCNICO OFICIAL
ADREMA: A10180471

GEOMETRÍA DEL SUELO

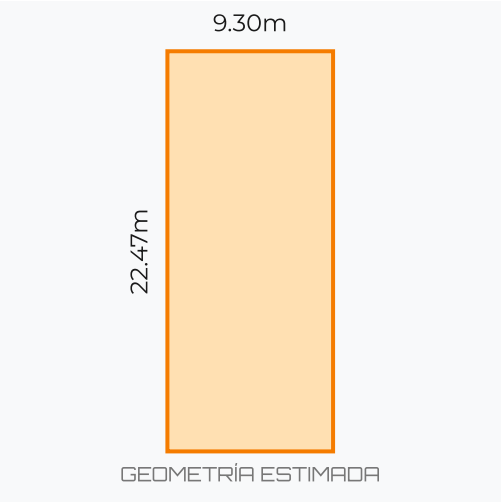

DISTRITO
CN

SUPERFICIE TOTAL
208.94 m²

FRENTE LOTE
9.3 m

INCIDENCIA ESTIMADA
Alta
MULTIPLICADOR DE SUELO

OCUPACIÓN (F.O.S.)

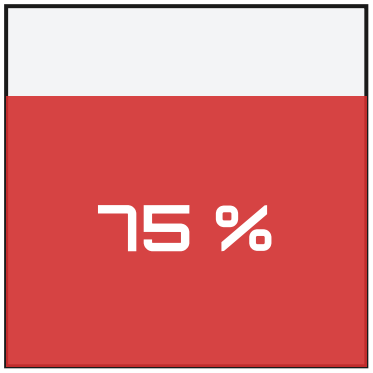

FOS: 0.75
Representación de ocupación
en Planta Baja

ENVOLVENTE VERTICAL NORMATIVA

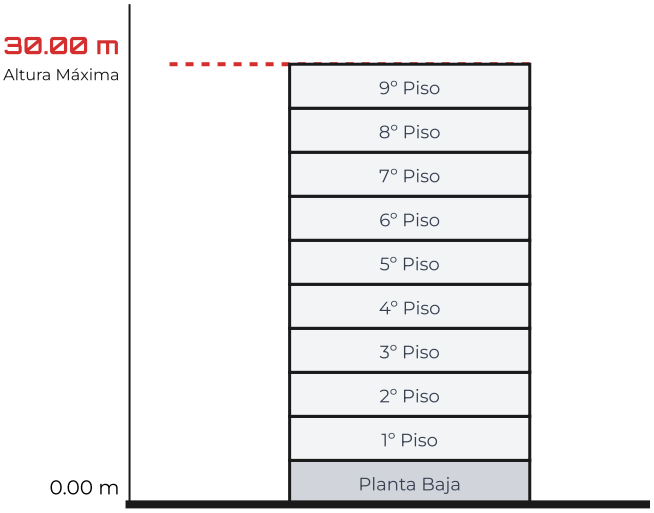

Potencial: PB + 9 Pisos

ANÁLISIS DE INTELIGENCIA ARTIFICIAL

La superficie de 208.94 m² y un FOS de 0.75 permiten una ocupación de 156.705 m², lo que ofrece oportunidades para edificaciones multifuncionales. La altura máxima de 30 m posibilita una estructura de varios niveles, ideal para viviendas o locales comerciales, contribuyendo a la densificación del área. Además, la ubicación estratégica sugiere un acceso óptimo a servicios y transporte, impulsando el desarrollo sostenible y la revitalización del entorno urbano.

POTENCIAL CONSTRUCTIVO

PB + 9 PISOS ALTOS (30m)

TABLA DE VALUACIÓN PRELIMINAR

INDICADOR	VALOR ESTIMADO
Sup. Vendible Estimada (bruta)	**1136.80 m²**
Costo Construcción	U$S 1050 / m²
Ticket Venta Promedio	U$S 2100 / m²
RENTABILIDAD BRUTA	**ALTO POTENCIAL**

CONCLUSIÓN FINAL

La altura máxima de 30m, con una estimación conservadora de 3m por nivel, permite la construcción de un edificio de 10 plantas (Planta Baja + 9 pisos tipo). Asumiendo una ocupación similar en las plantas superiores, la superficie bruta total estimada ascendería a 1421.00 m². Aplicando un factor de eficiencia del 80% para obtener la superficie vendible, se proyectan aproximadamente 1136.80 m² de superficie comercializable. Un costo de construcción promedio de U$S 1050/m² (valor extraído de la planilla "TABLA DE VALUACIÓN PRELIMINAR") y venta de U$S 2100/m² (valor extraído de la planilla "TABLA DE VALUACIÓN PRELIMINAR"), el costo total ascendería a U$S 1.492.050 y los ingresos por venta a U$S 2.387.280. Esto arroja un margen bruto significativo de U$S 895.230.