INFORME TÉCNICO OFICIAL
ADREMA: A10690561

GEOMETRÍA DEL SUELO

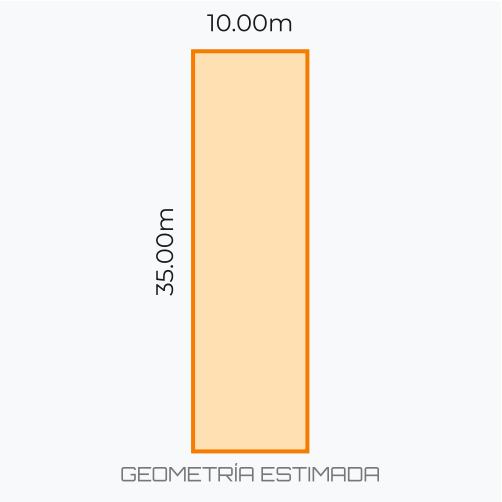

DISTRITO
EM.2

SUPERFICIE TOTAL
350 m²

FRENTE LOTE
10 m

INCIDENCIA ESTIMADA
Media
MULTIPLICADOR DE SUELO

OCUPACIÓN (F.O.S.)



FOS: 0.7
Representación de ocupación
en Planta Baja

ENVOLVENTE VERTICAL NORMATIVA

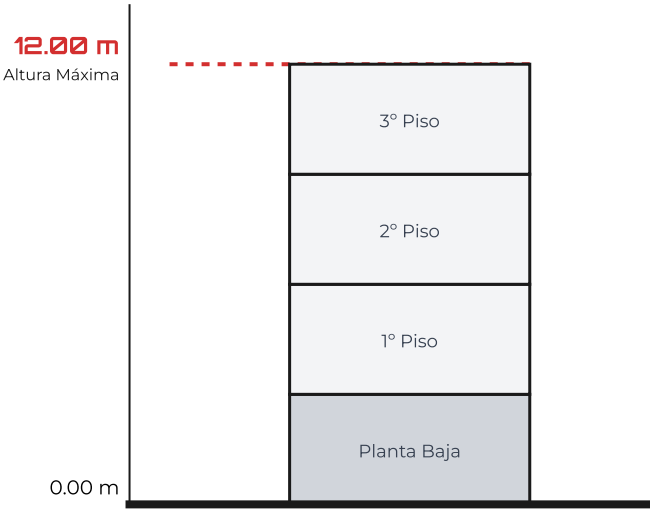

Potencial: PB + 3 Pisos

ANÁLISIS DE INTELIGENCIA ARTIFICIAL

El terreno cuenta con un frente de 10 m. Según normativa, se deben considerar retiros de 3 m en el frente y 1.5 m en los laterales, permitiendo un diseño que respete la volumetría y la integración con el entorno urbano. El fondo no requiere retiro.

POTENCIAL CONSTRUCTIVO

PB + 3 PISOS ALTOS (12m)

TABLA DE VALUACIÓN PRELIMINAR

INDICADOR	VALOR ESTIMADO
Sup. Vendible Estimada (bruta)	**1400.00 m²**
Costo Construcción	U$S 1050 / m²
Ticket Venta Promedio	U$S 2100 / m²
RENTABILIDAD BRUTA	**ALTO POTENCIAL**

CONCLUSIÓN FINAL

La partida A10690561 presenta una superficie de 350 m² y un FOS de 0.7, permitiendo un área construida de 245 m². La altura máxima de 12 m es adecuada para un desarrollo urbano compacto.