INFORME TÉCNICO OFICIAL
ADREMA: A10020941

PROPIETARIO: VER MENSURA ADJUNTA

UBICACIÓN: CONSULTAR DOCUMENTACIÓN

GEOMETRÍA DEL SUELO

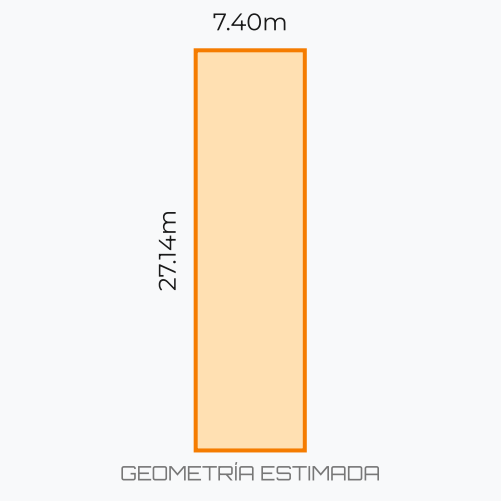

DISTRITO
CN

SUPERFICIE TOTAL
200.84 m²

FRENTE LOTE
7.4 m

INCIDENCIA ESTIMADA
ALTA
MULTIPLICADOR DE SUELO

OCUPACIÓN (F.O.S.)

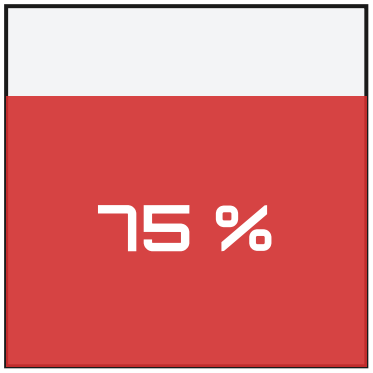

FOS: 0.75
Representación de ocupación
en Planta Baja

ENVOLVENTE VERTICAL NORMATIVA

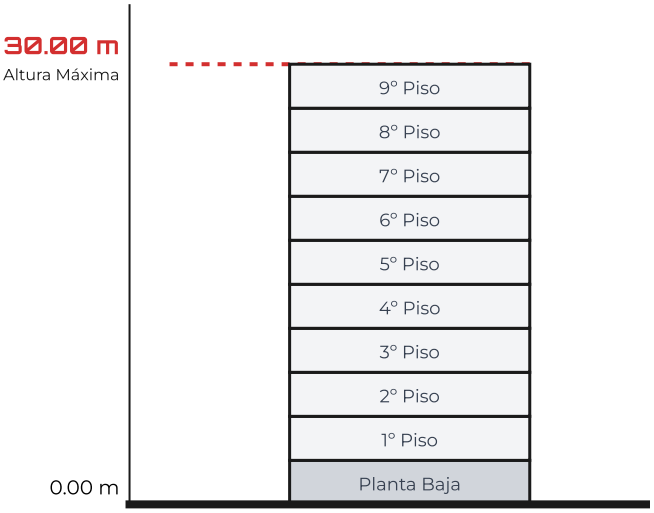

Potencial: PB + 9 Pisos

ANÁLISIS DE INTELIGENCIA ARTIFICIAL

El análisis urbanístico de la partida A10020941 revela un potencial significativo para el desarrollo sostenible. La superficie de 200.84 m² y el FOS de 0.75 sugieren una edificabilidad de 151 m², ideal para proyectos que integren áreas comerciales y residenciales. La altura máxima de 30 m permite aprovechar la verticalidad, enriqueciendo el paisaje urbano. La ubicación estratégica del distrito CN Sup. Parcela: 200.84 m² Frente: 7.4 m favorece la conectividad, mientras que el frente de 7.4 m facilita un acceso fluido. Se recomienda fomentar el diseño innovador que respete el entorno y promueva la cohesión social.

POTENCIAL CONSTRUCTIVO

PB + 9 PISOS ALTOS (30m)

TABLA DE VALUACIÓN PRELIMINAR

INDICADOR	VALOR ESTIMADO
Sup. Vendible Estimada (bruta)	**1092.80 m²**
Costo Construcción	U$S 1050 / m²
Ticket Venta Promedio	U$S 2100 / m²
RENTABILIDAD BRUTA	**ALTO POTENCIAL**

CONCLUSIÓN FINAL

La altura máxima de 30m, con una estimación conservadora de 3m por nivel, permite la construcción de un edificio de 10 plantas (Planta Baja + 9 pisos tipo). Asumiendo una ocupación similar en las plantas superiores, la superficie bruta total estimada ascendería a 1366.00 m². Aplicando un factor de eficiencia del 80% para obtener la superficie vendible, se proyectan aproximadamente 1092.80 m² de superficie comercializable. Un costo de construcción promedio de U$S 1050/m² (valor extraído de la planilla "TABLA DE VALUACIÓN PRELIMINAR") y venta de U$S 2100/m² (valor extraído de la planilla "TABLA DE VALUACIÓN PRELIMINAR"), el costo total ascendería a U$S 1.434.300 y los ingresos por venta a U$S 2.294.880. Esto arroja un margen bruto significativo de U$S 860.580.

18505-U

DISPOSICION Nº 110– ART. 2g)

"EL PRESENTE PLANO DE MENSURA SE REGISTRA AL SOLO Y UNICO EFECTO DE APORTAR AL JUEZ QUE ENTENDERA EN EL EVENTUAL JUICIO DE USUCAPION LOS ELEMENTOS DE LA PARCELA QUE DICE SER POSEÍDA, AL MOMENTO DE REALIZARSE LAS OPERACIONES DE MENSURA, NO PUDIENDO POR LO TANTO SERVIR DE BASE PARA LA TRANSFERENCIA DE DOMINIO, PREVIA SENTENCIA JUDICIAL".

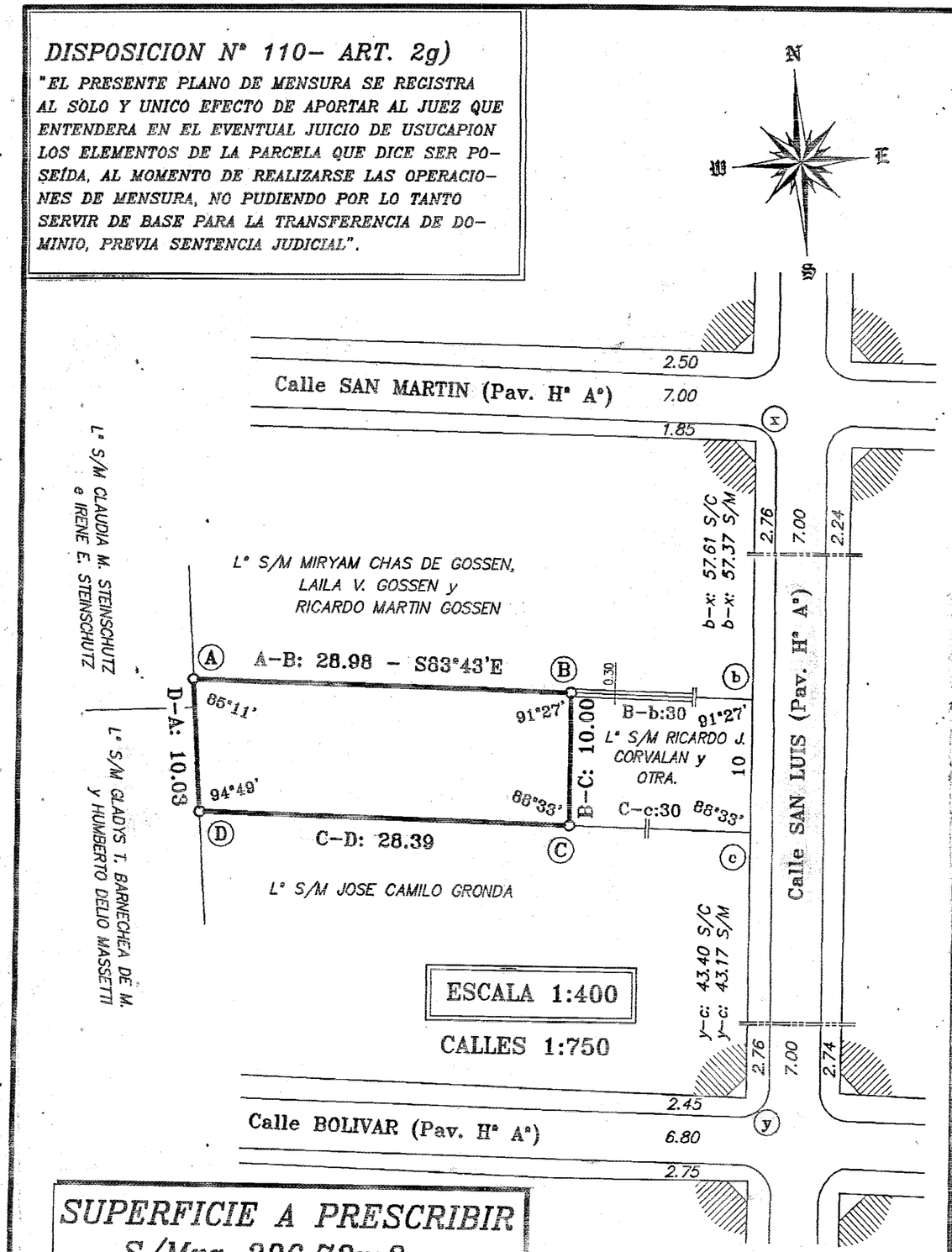

SUPERFICIE A PRESCRIBIR
S/Mra 286,73m2

NOTAS:

- Las medidas lineales están expresadas en metros.
- Rumbo adoptado del lado (B–C): N83°43'O Mra. 10665–U, para el lado (A–B) de estas operaciones.
- Estas operaciones se superponen al polígono a–D–C–b–a, de la Mensura 10665–U.
- Estas operaciones se superponen parcialmente a la Mra. 2452–U.
- Los poseedores del inmueble objeto del presente trabajo acceden a la vía pública a través del inmueble que limita al Este, cuyo dominio les pertenece, y queda acreditado según informe del Registro de la Propiedad Inmueble que adjunto al expediente.

REFERENCIAS:

- Muros.
- Linea de mensura.
- Mojón de madera colocado.
- Edificación existente
- S/M Según Mensura.
- S/C Según Catastro.

Objeto: MENSURA PARA PRESCRIPCION ADQUISITIVA

Mensura Nº 18505-U

Nomenclatura Catastral

Carácter: Particular

Provincia de Corrientes – República Argentina

Departamento: CAPITAL.

Lugar: Planta Urbana de la Ciudad de Corrientes.

Posesión de:

Ricardo Jorge CORVALAN y María Emilia del Pilar GRONDA

Ubicación: Manzana Nº 239, Parcela Nº 40, Bº "CAMBA CUA"

PARTIDA INMOBILIARIA: A1–2094–1

PROPIEDAD DE: LA PIA UNION DE SAN ANTONIO DE PADUA. (IGLESIA DE SAN FRANCISCO).

Dominio: Insc. Reg. Prop. Pcia.: Tº 401, Fº 116.529 vto., Fca. 1639, Año 1937.
Insc. Reg. Prop. Mpal.: NO SE ENCONTRO.

PARTIDA INMOBILIARIA: A1–2094–1.

Mensuras Relacionadas: 2452–U; 3140–U; 10665–U.

APROBADO EXCLUSIVAMENTE EN EL ASPECTO GEOMETRICO

CROQUIS DE UBICACION

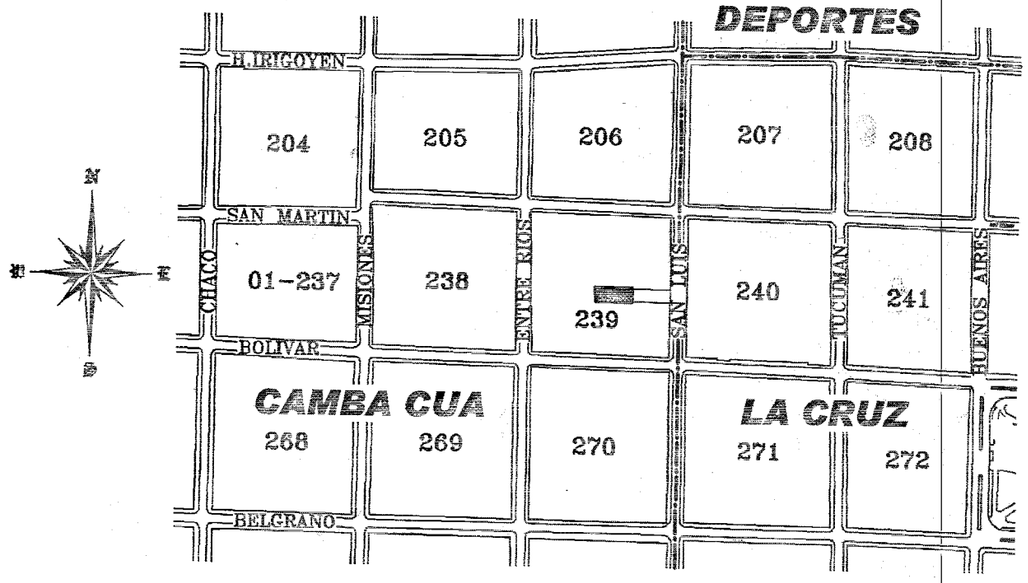

Corrientes, Capital, 10 de Febrero de 2006.

Los elementos consignados en el presente plano son de exclusiva responsabilidad del profesional actuante.

ALICIA CECILIA CANEVARO	RICARDO J. CORVALAN	MARIA E. del P. GRONDA
Agrimensor Nacional	POSEEDOR	POSEEDORA
M.C.P. 2049 – D.G.C. 750	DNI 13.579.731	DNI 16.357.480
Dom. Bolívar Nº 558 – Ctes.	Dom. San Luis Nº 1170 – Ctes.	Dom. San Luis Nº 1170 – Ctes.

DIG

OBJETO: MENSURA Y UNIFICACION

CARACTER: PARTICULAR

PROVINCIA DE CORRIENTES (REP. ARGENTINA)

DEPARTAMENTO: CAPITAL

LUGAR: Planta Urbana - Ciudad de CORRIENTES

MENSURA Nº 26753-"U"

NOM. CATASTRAL

PROPIEDAD DE:

50%RICARDO JORGE CORVALAN y 50% MARIA EMILIA DEL PILAR GRONDA

UBICACION: Manzana Nº 239 - Parcelas 40 y 41 s/Cat. Barrio "CAMBA CUA"

DOMINIO: Reg. Prop. Pcia. : Parc. 40 - Folio Real - Matrícula 60095 - Año: 2.015

Parc. 41 - Folio Real - Matrícula 48895 - Año: 2.006

Reg. Prop. Munic.: Parc. 40 - Tº 1 - Fº 1 - Fca. 1 - Lº 5 - Año: 2.015

Reg. Prop. Munic.: Parc. 41 - Tº 2 - Fº 334 - Fca. 252 - Lº 5 - Año: 2.006

Partidas Inmobiliarias: Parc. 40 - A1-2094-1, Parc.41 - A1-15250-1

MRAS. RELACIONADAS: 2452-U, 3140-U, 10665-U, 18505-U

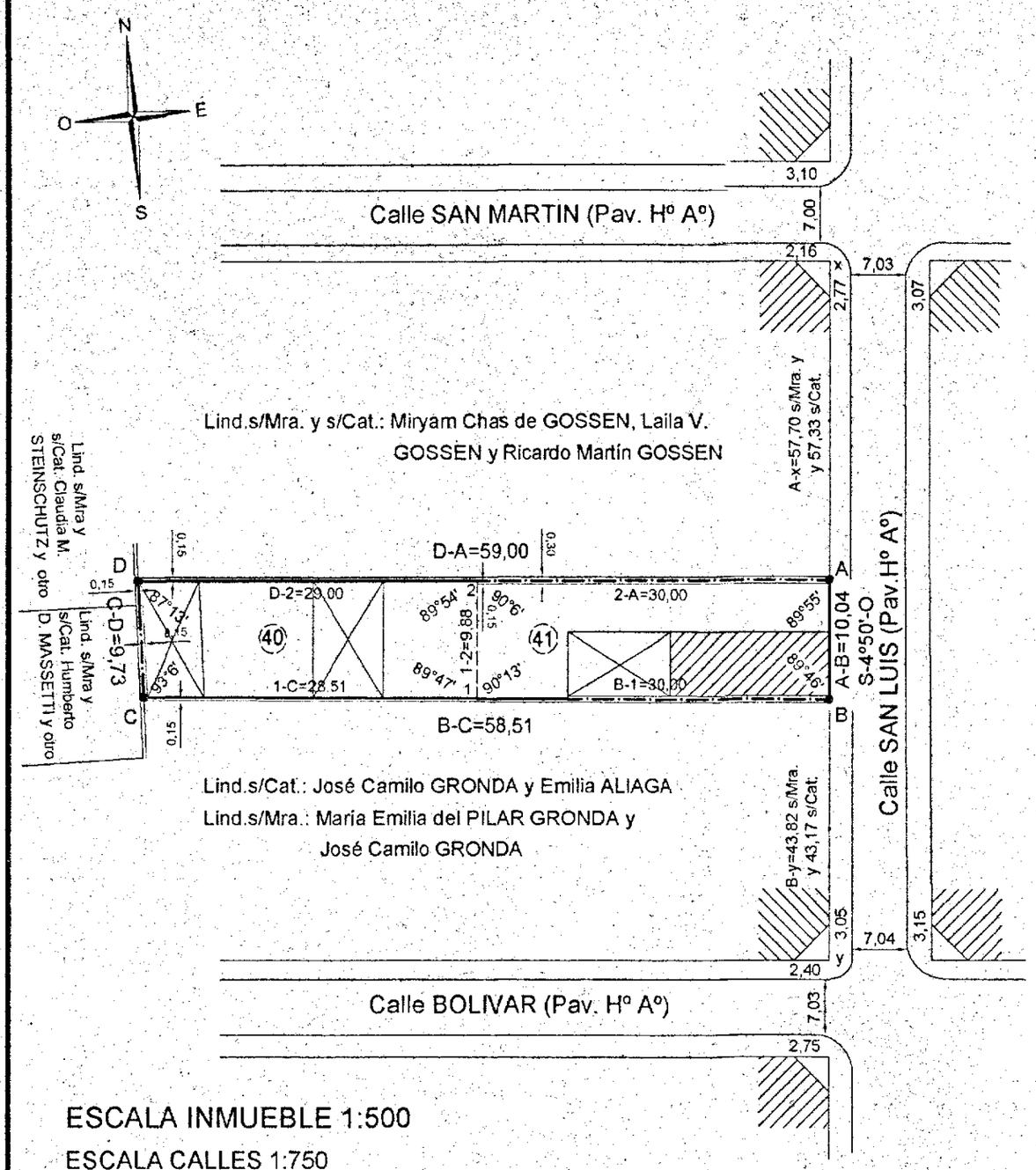

ESCALA INMUEBLE 1:500

ESCALA CALLES 1:750

BALANCE DE SUPERFICIES

TITULO Parc. 41		TITULO Parc. 40	
Sup. s/Tit. (calc.):	300,00 m2	Sup. s/Tit.:	286,73 m2
Sup. s/Mra.: - - -	298,75 m2	Sup. s/Mra.:	281,78 m2
Diferencia en (-) :	1,25 m2	Dif. en (-) :	4,95 m2

UNIFICACION S/MENSURA

Sup. Parcela 41 : 298,75 m2

Sup. Parcela 40 : 281,78 m2

Sup. Unificada : 580,53 m2 | Part. Inmob.: A1-2094-1

REFERENCIAS:

- • Roblón de hierro colocado
- Linea de mensura
- Muros
- Edificación
- Pared medianera

NOTAS:

1) Todas las medidas lineales en metros.
2) Rumbo adoptado del lado A-B de la Mra. 10665-U para el lado A-B de las presentes operaciones.
3) Las presentes operaciones se superpone con la mensura 10665-U y parcialmente con la mensura 18505-U

CROQUIS DE UBICACION

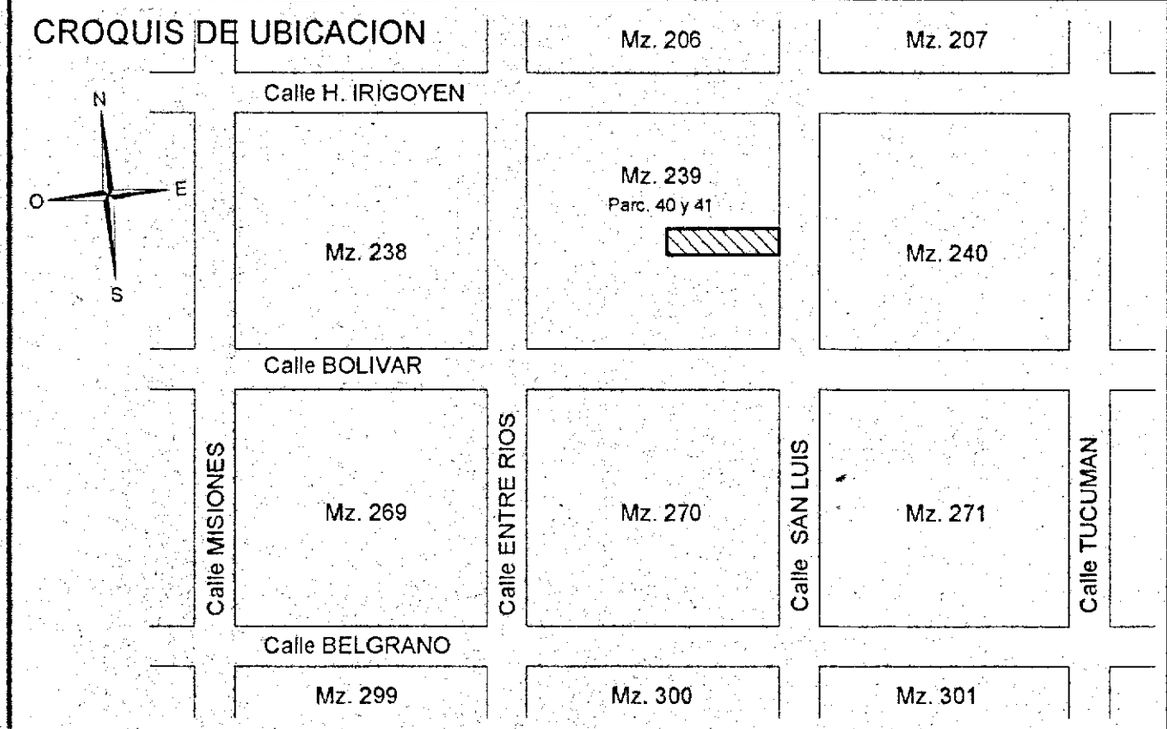

CORRIENTES, 13 de enero de 2.017.-

RAUL ROBERTO RUVEDA	RICARDO J. CORVALAN	MARIA E. del P. GRONDA
Agrimensor Nacional	Propietario	Propietaria
Mat. Prof. 2009 - D.G.C. y C. 742	D.N.I.Nº 11.146.819	D.N.I.Nº 16.357.480
Domic. Gob. Lagraña Nº 279 - Ctes.-	Domic.: San Luis Nº 1170 - Ctes.-	Domic.: San Luis Nº 1170 - Ctes.-

MARTA H. BELCASTRO
AGRIMENSOR NACIONAL
Dcción. Gral. de Catastro y Cartografía

DIRECCION GENERAL DE CATASTRO Y CARTOGRAFIA
PROVINCIA DE CORRIENTES
MENSURA REGISTRADA
CON EL Nº 26753-"U"
ETER. 20 DE 03 DE 2017

OBJETO: MENSURA, PROYECTO DE UNIFICACION Y REDISTRIBUCION PARCELARIA

MENSURA Nº 29864'U

NOM. CATASTRAL

CARACTER: PARTICULAR

PROVINCIA DE CORRIENTES (REP. ARGENTINA)

DEPARTAMENTO: CAPITAL

LUGAR: Planta Urbana - Ciudad de CORRIENTES

PROPIEDAD DE: Tít. 1 - RICARDO JORGE CORVALAN y MARIA EMILIA DEL PILAR GRONDA

PROPIEDAD DE: Tít. 2 - EMILIA ALIAGA DE GRONDA y JOSE CAMILO GRONDA

UBICACION: Manzana Nº 239 - Parcelas 40, 41 y 42 s/Cat. Barrio "CAMBA CUA"

DOMINIO: Reg. Prop. Pcia. : Tít. 1 - Parc. 40 - Folio Real - Matrícula 60095 - Año: 2.015
y Parc. 41 - Folio Real - Matrícula 48895 - Año: 2.006
Tít. 2 - Parc. 42 - Tº 4 - Fº 953 - Nº 750 - Año: 1.970
Reg. Prop. Munic.: Tít. 1 - Parc. 40 - Tº 1 - Fº 1 - Fca. 1 - Lº 5 - Año: 2.015
y Parc. 41 - Tº 2 - Fº 334 - Fca. 252 - Lº 5 - Año: 2.006
Tít. 2 - Parc. 42 - Tº 5 - Fº 847 - Fca. 795 - Lº 9 - Año: 1.970
Partidas Inmobiliarias: Parc. 40 y 41 A1-2094-1, Parc.42 - A1-10192-1

MRAS. RELACIONADAS: 2452-U, 3140-U, 10665-U, 18505-U, 26753-U

CROQUIS S/TITULO

Fuera de Escala

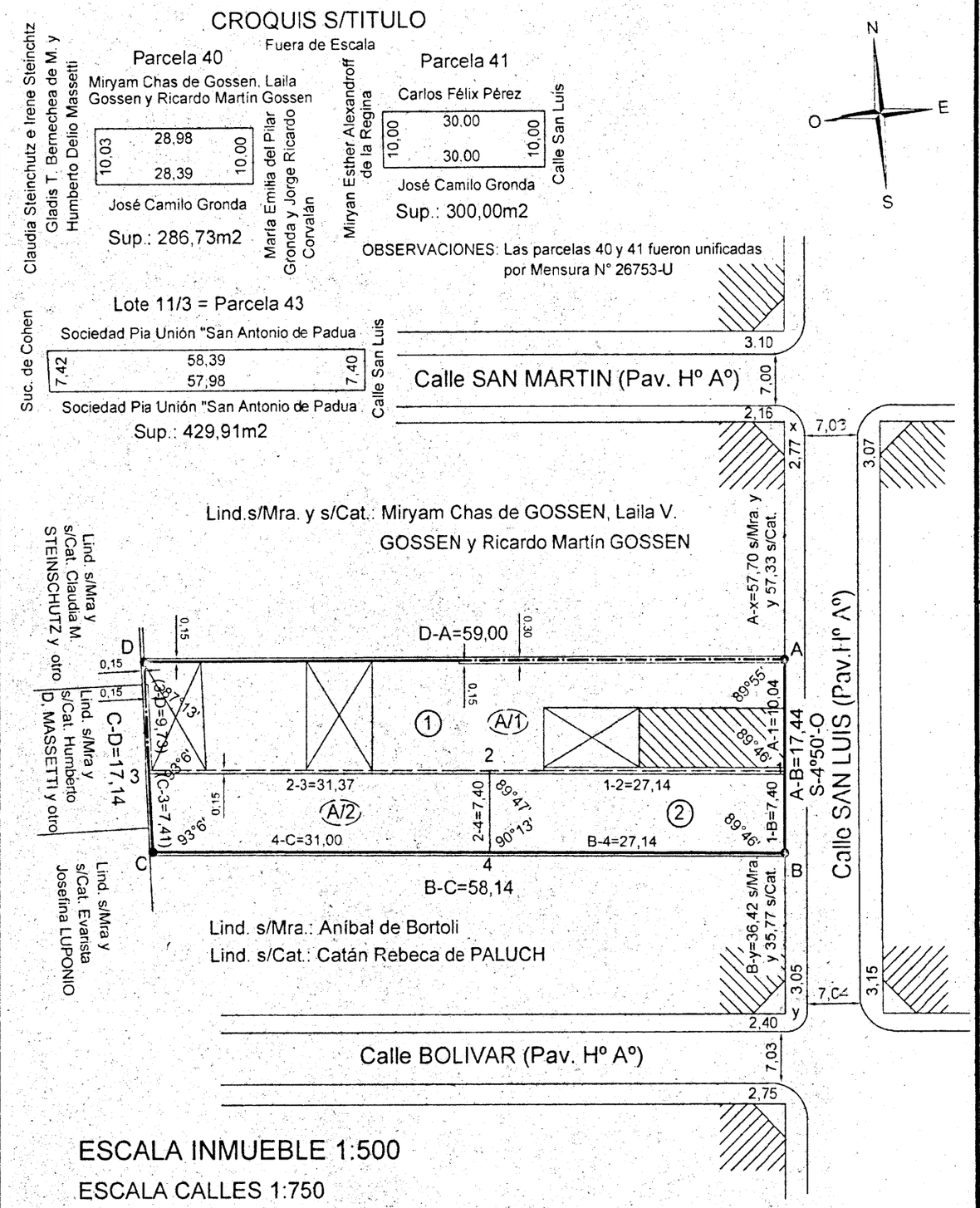

ESCALA INMUEBLE 1:500

ESCALA CALLES 1:750

SUPERFICIE SEGUN UNIFICACION

Sup. s/planilla = 1.012,03 m2

REDISTRIBUCION PARCELARIA

Sup. Parcela A/1 : 580,41 m2

Sup. Parcela A/2 : 230,77 m2

Sup. Parcela 1 : 811,18 m2

Sup. Parcela 2 : 200,84 m2

REFERENCIAS:

- Roblón de hierro colocado
- Linea de mensura
- Muros
- Edificación
- Pared medianera

NOTAS:

1) Todas las medidas lineales en metros.
2) Rumbo adoptado del lado A-B de la Mra. 10665-U para el lado A-B de las presentes operaciones.
3) Las presentes operaciones se superpone con la mensura 10665-U y parcialmente con la mensura 18505-U
4) Las presentes operaciones se autorizó por vía de excepción según Ordenanza 6969/2020 y Resolución N° 3285/2020
5) El presente plano de Mensura, Proyecto de Unificación y Redistribución Parcelaria fue visado por la Municipalidad de la Ciudad de Corrientes por Exte. 567-G-2.018

CROQUIS DE UBICACION

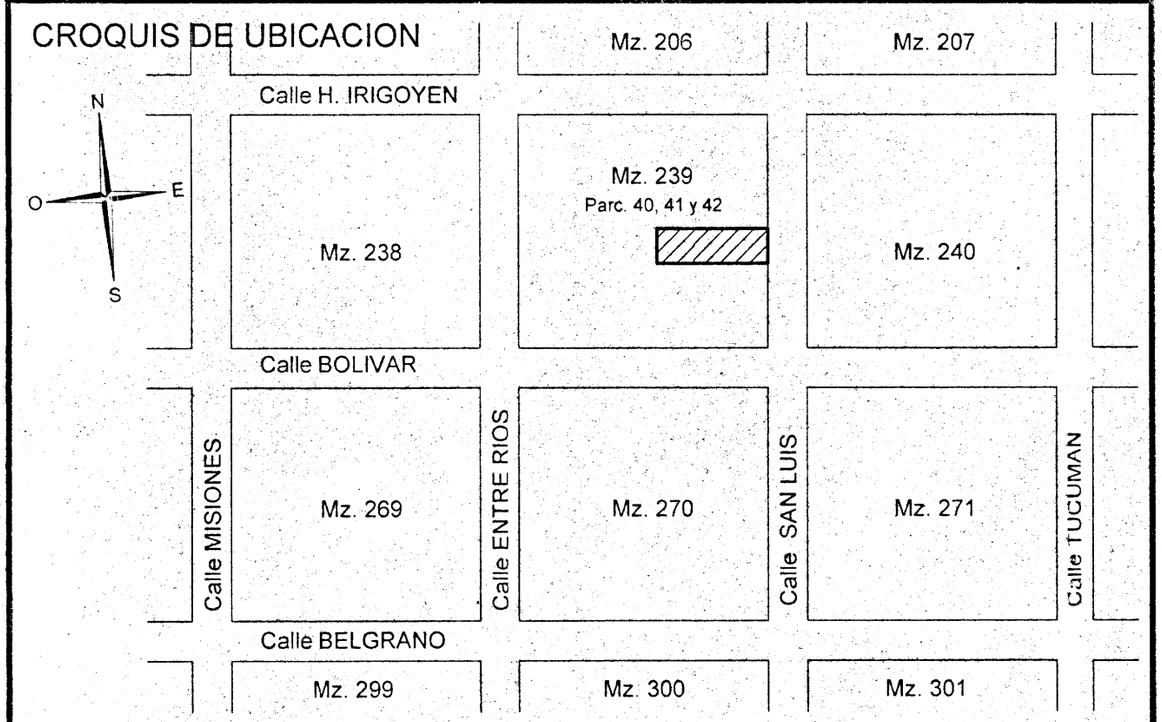

CORRIENTES, 04 de junio de 2.021.-

RAUL ROBERTO RUVEDA
Agrim. Nacional
M.C.P. 2009 - D.G.C y C. 742
Domic.: Gob. Lagraña Nº 279 - Ctes.-

MINISTERIO DE HACIENDA Y FINANZAS - DIRECCION GENERAL DE CATASTRO - CORRIENTES

MARIA EMILIA del P. GRONDA
Propietaria y P/A
D.N.I.Nº 16.357.480
Domic.: San Luis Nº 1170 - Ctes.-

MARTA H. BALCASTRO
AGRIMENSOR NACIONAL
Dección. Gral. de Catastro y Cartografía

DIRECCION GENERAL DE CATASTRO Y CARTOGRAFIA
PROVINCIA DE CORRIENTES
MENSURA REGISTRADA
CON EL Nº 29864'U
CTES. 04 DE agosto DE 2021.