INFORME TÉCNICO OFICIAL
ADREMA: A10045711

PROPIETARIO: GARCIA NAVARRETE ISABEL

UBICACIÓN: DEPARTAMENTO: CAPITAL - LOCALIDAD: CAPITAL - SECCIÓN: - - CALLE: SAN LUIS - NRO: 1064 - MANZANA: 0206 - LOTE: 05

GEOMETRÍA DEL SUELO

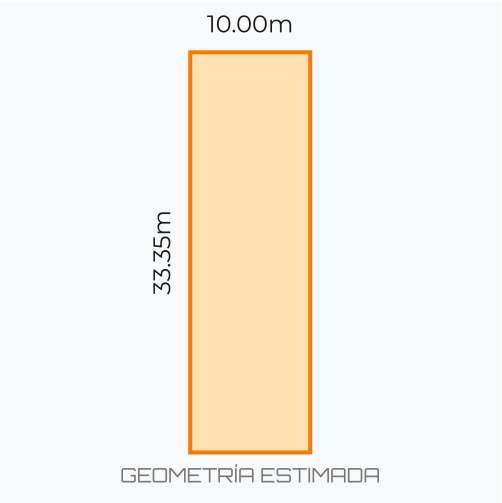

DISTRITO
CN

SUPERFICIE TOTAL
333.5 m²

FRENTE LOTE
10 m

INCIDENCIA ESTIMADA
ALTA
MULTIPLICADOR DE SUELO

OCUPACIÓN (F.O.S.)

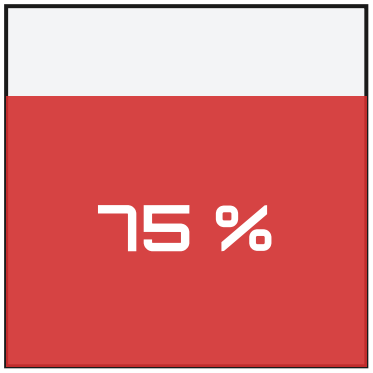

FOS: 0.75
Representación de ocupación
en Planta Baja

ENVOLVENTE VERTICAL NORMATIVA

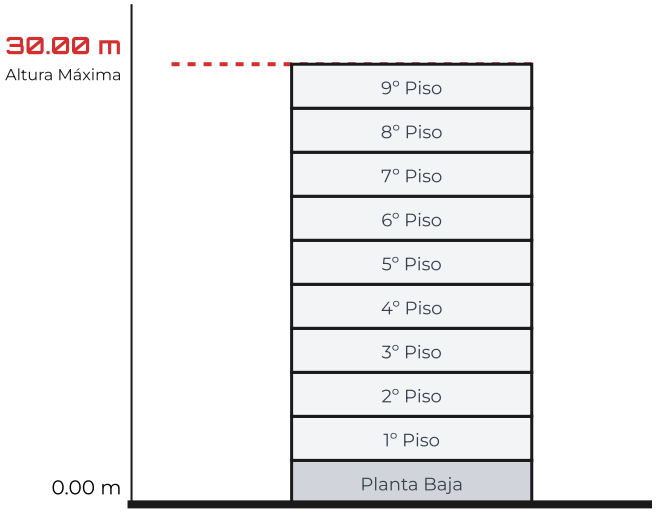

Potencial: PB + 9 Pisos

ANÁLISIS DE INTELIGENCIA ARTIFICIAL

El análisis urbanístico de la partida A10045711 revela un potencial significativo para el desarrollo sostenible. La superficie de 333.5 m² y el FOS de 0.75 sugieren una edificabilidad de 250 m², ideal para proyectos que integren áreas comerciales y residenciales. La altura máxima de 30 m permite aprovechar la verticalidad, enriqueciendo el paisaje urbano. La ubicación estratégica del distrito CN Sup. Parcela: 333.5 m² Frente: 10 m favorece la conectividad, mientras que el frente de 10 m facilita un acceso fluido. Se recomienda fomentar el diseño innovador que respete el entorno y promueva la cohesión social.

POTENCIAL CONSTRUCTIVO

PB + 9 PISOS ALTOS (30m)

TABLA DE VALUACIÓN PRELIMINAR

INDICADOR	VALOR ESTIMADO
Sup. Vendible Estimada (bruta)	**1814.40 m²**
Costo Construcción	U$S 1050 / m²
Ticket Venta Promedio	U$S 2100 / m²
RENTABILIDAD BRUTA	**ALTO POTENCIAL**

CONCLUSIÓN FINAL

La altura máxima de 30m, con una estimación conservadora de 3m por nivel, permite la construcción de un edificio de 10 plantas (Planta Baja + 9 pisos tipo). Asumiendo una ocupación similar en las plantas superiores, la superficie bruta total estimada ascendería a 2268.00 m². Aplicando un factor de eficiencia del 80% para obtener la superficie vendible, se proyectan aproximadamente 1814.40 m² de superficie comercializable. Un costo de construcción promedio de U$S 1050/m² (valor extraído de la planilla "TABLA DE VALUACIÓN PRELIMINAR") y venta de U$S 2100/m² (valor extraído de la planilla "TABLA DE VALUACIÓN PRELIMINAR"), el costo total ascendería a U$S 2.381.400 y los ingresos por venta a U$S 3.810.240. Esto arroja un margen bruto significativo de U$S 1.428.840.

Referencias:

- Mojòn de hierro encontrado.-
- Mojón de hierro colocado.-
- Linea de Mensura.-
- Edificación existente.-
- Muros existentes.-
- Muro bajo con rejas.-
- Columna de H° A°.-

Notas:

- Medidas lineales dadas en metros.-
- Rumbo Magnetico medido lado A-B=N-82°31'-O, del presente trabajo.-
- Calles: Escala 1 : 750.-
- Los vertices B; C y D, del presente trabajo estan perfectamente materializados con muros existentes.-
- La Linea Municipal se tomo teniendo en cuenta el mojon de H° encontrado en las esquinas de las Calles San Luis e Hirigoyen, con la edificacion existente sobre calle objeto del presente trabajo.-

Balance de Superficies

Sup. S/Titulo (Calculada)	333,50 m2
Sup. S/Mensura	334,72 m2
Diferencia en (+)	1,22 m2

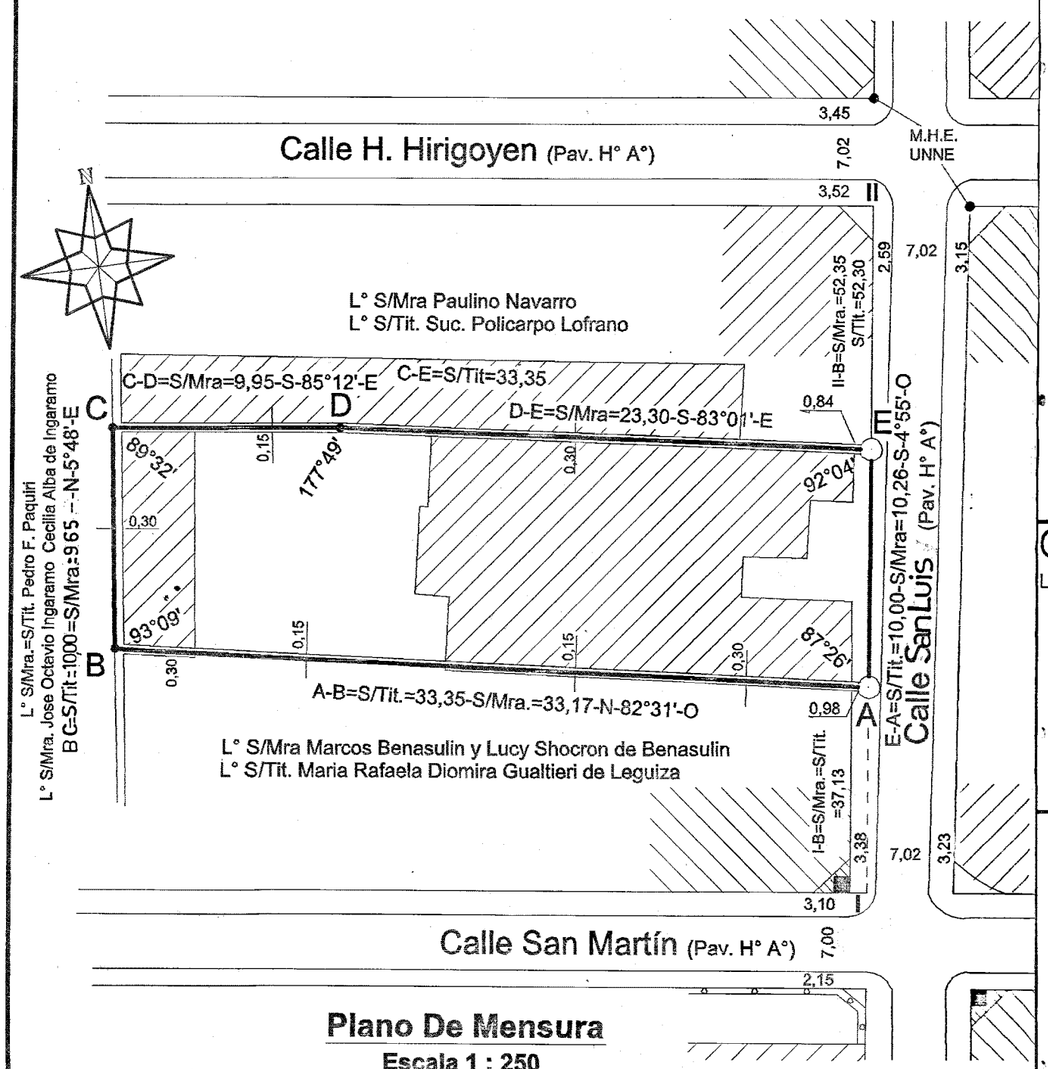

Plano De Mensura

Escala 1 : 250

Objeto: **Mensura .-**

Caracter: **P a r t i c u l a r .-**

Provincia De **CORRIENTES** - Rep. Argentina.-

Departamento: **C a p i t a l .-**

Lugar: **Ciudad de Corrientes.-**

Mensura Nº 17.766-U

Nomenclatura Catastral

Propietario:

Isabel Marta GARCIA NAVARRETE

Ubicaciòn: **Manz. N° 206 - Lote N° 5 S/Tit. y Lote N° 18 - S/Cat "B° Camba Cua".-**

Dominio: **Reg. Prop. Prov.**: F° Real Mat. N°10.245 - Año 1.981.-

Reg. Prop. Munic.: L°4 - T° 24 - N° 356 - F° 388 - Año 1.981.-

Adrema: **A1 - 4.571 - 1.-**

Mensuras Relacionadas: 3.715-U.-

Croquis de Ubicaciòn:

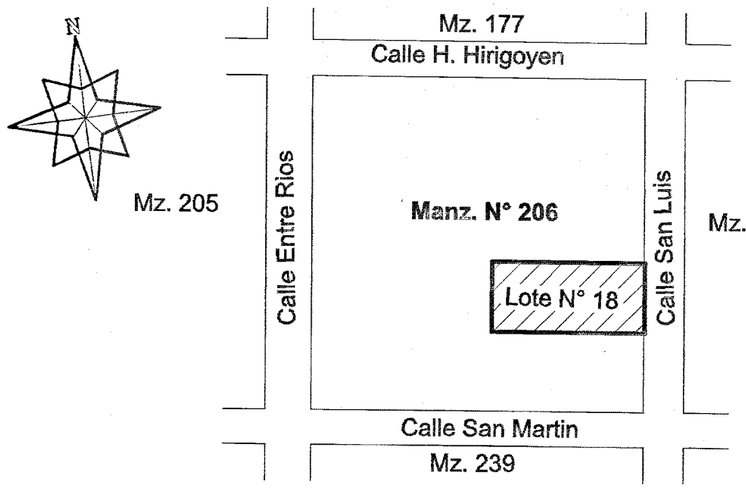

Corrientes; Capital; 22 de Septiembre de 2.004.-

Los elementos consignados en el presente expediente son de exclusiva responsabilidad del profesional actuante.-

EDUARDO ZIBECCHI
Agrimensor Nacional
C.P.Nº 2.458 - D.G.C.Nº 814
Calle Sicilia N° 5.030 - Ctes.-

ISABEL MARTA GARCIA NAVARRETE
Propietaria
D.N.I. N° 12.440.682
Dom.: San Luis N° 1.074 - Ctes.