INFORME TÉCNICO OFICIAL
ADREMA: A101101921

PROPIETARIO: CONSULTAR REGISTRO

UBICACIÓN: VER MENSURA ADJUNTA

GEOMETRÍA DEL SUELO

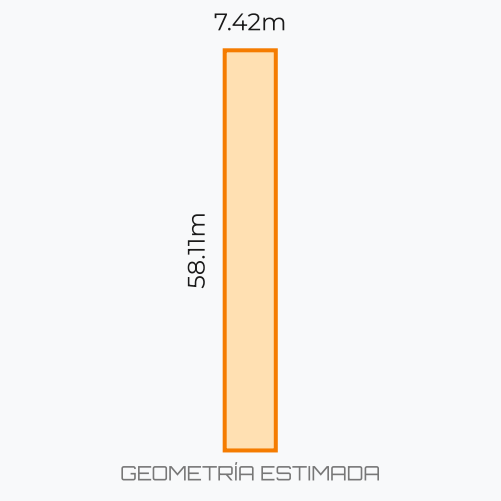

DISTRITO
CN

SUPERFICIE TOTAL
431.15 m²

FRENTE LOTE
7.42 m

INCIDENCIA ESTIMADA
ALTA
MULTIPLICADOR DE SUELO

OCUPACIÓN (F.O.S.)

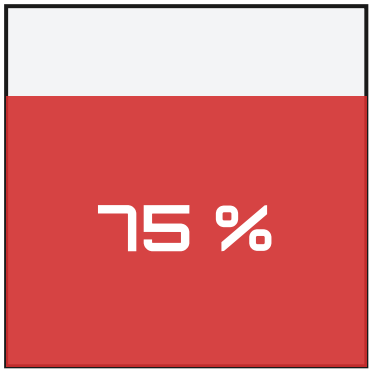

FOS: 0.75
Representación de ocupación
en Planta Baja

ENVOLVENTE VERTICAL NORMATIVA

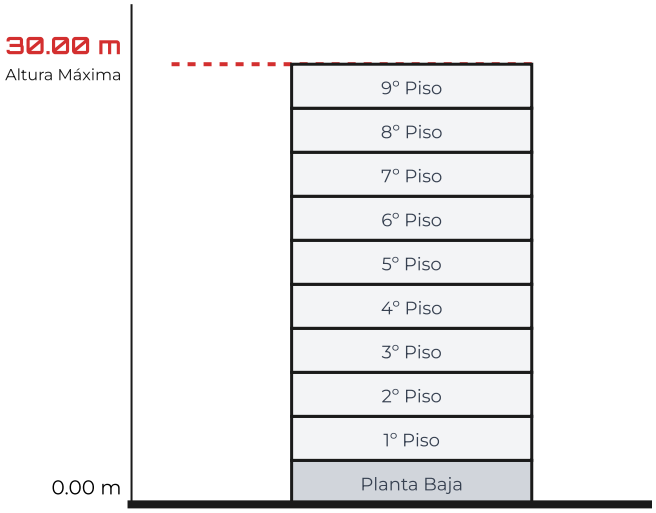

Potencial: PB + 9 Pisos

ANÁLISIS DE INTELIGENCIA ARTIFICIAL

El análisis urbanístico de la partida A10101921 revela un potencial significativo para el desarrollo sostenible. La superficie de 431.15 m² y el FOS de 0.75 sugieren una edificabilidad de 323 m², ideal para proyectos que integren áreas comerciales y residenciales. La altura máxima de 30 m permite aprovechar la verticalidad, enriqueciendo el paisaje urbano. La ubicación estratégica del distrito CN Sup. Parcela: 431.15 m² Frente: 7.42 m favorece la conectividad, mientras que el frente de 7.42 m facilita un acceso fluido. Se recomienda fomentar el diseño innovador que respete el entorno y promueva la cohesión social.

POTENCIAL CONSTRUCTIVO

PB + 9 PISOS ALTOS (30m)

TABLA DE VALUACIÓN PRELIMINAR

INDICADOR	VALOR ESTIMADO
Sup. Vendible Estimada (bruta)	**2345.60 m²**
Costo Construcción	U$S 1050 / m²
Ticket Venta Promedio	U$S 2100 / m²
RENTABILIDAD BRUTA	**ALTO POTENCIAL**

CONCLUSIÓN FINAL

La altura máxima de 30m, con una estimación conservadora de 3m por nivel, permite la construcción de un edificio de 10 plantas (Planta Baja + 9 pisos tipo). Asumiendo una ocupación similar en las plantas superiores, la superficie bruta total estimada ascendería a 2932.00 m². Aplicando un factor de eficiencia del 80% para obtener la superficie vendible, se proyectan aproximadamente 2345.60 m² de superficie comercializable. Un costo de construcción promedio de U$S 1050/m² (valor extraído de la planilla "TABLA DE VALUACIÓN PRELIMINAR") y venta de U$S 2100/m² (valor extraído de la planilla "TABLA DE VALUACIÓN PRELIMINAR"), el costo total ascendería a U$S 3.078.600 y los ingresos por venta a U$S 4.925.760. Esto arroja un margen bruto significativo de U$S 1.847.160.

OBJETO: MENSURA, PROYECTO DE UNIFICACION Y REDISTRIBUCION PARCELARIA

MENSURA Nº 29864'U

NOM. CATASTRAL

CARACTER: PARTICULAR

PROVINCIA DE CORRIENTES (REP. ARGENTINA)

DEPARTAMENTO: CAPITAL

LUGAR: Planta Urbana - Ciudad de CORRIENTES

PROPIEDAD DE: Tít. 1 - RICARDO JORGE CORVALAN y MARIA EMILIA DEL PILAR GRONDA

PROPIEDAD DE: Tít. 2 - EMILIA ALIAGA DE GRONDA y JOSE CAMILO GRONDA

UBICACION: Manzana Nº 239 - Parcelas 40, 41 y 42 s/Cat. Barrio "CAMBA CUA"

DOMINIO: Reg. Prop. Pcia. : Tít. 1 - Parc. 40 - Folio Real - Matrícula 60095 - Año: 2.015
y Parc. 41 - Folio Real - Matrícula 48895 - Año: 2.006
Tít. 2 - Parc. 42 - Tº 4 - Fº 953 - Nº 750 - Año: 1.970
Reg. Prop. Munic.: Tít. 1 - Parc. 40 - Tº 1 - Fº 1 - Fca. 1 - Lº 5 - Año: 2.015
y Parc. 41 - Tº 2 - Fº 334 - Fca. 252 - Lº 5 - Año: 2.006
Tít. 2 - Parc. 42 - Tº 5 - Fº 847 - Fca. 795 - Lº 9 - Año: 1.970
Partidas Inmobiliarias: Parc. 40 y 41 A1-2094-1, Parc.42 - A1-10192-1

MRAS. RELACIONADAS: 2452-U, 3140-U, 10665-U, 18505-U, 26753-U

CROQUIS S/TITULO

Fuera de Escala

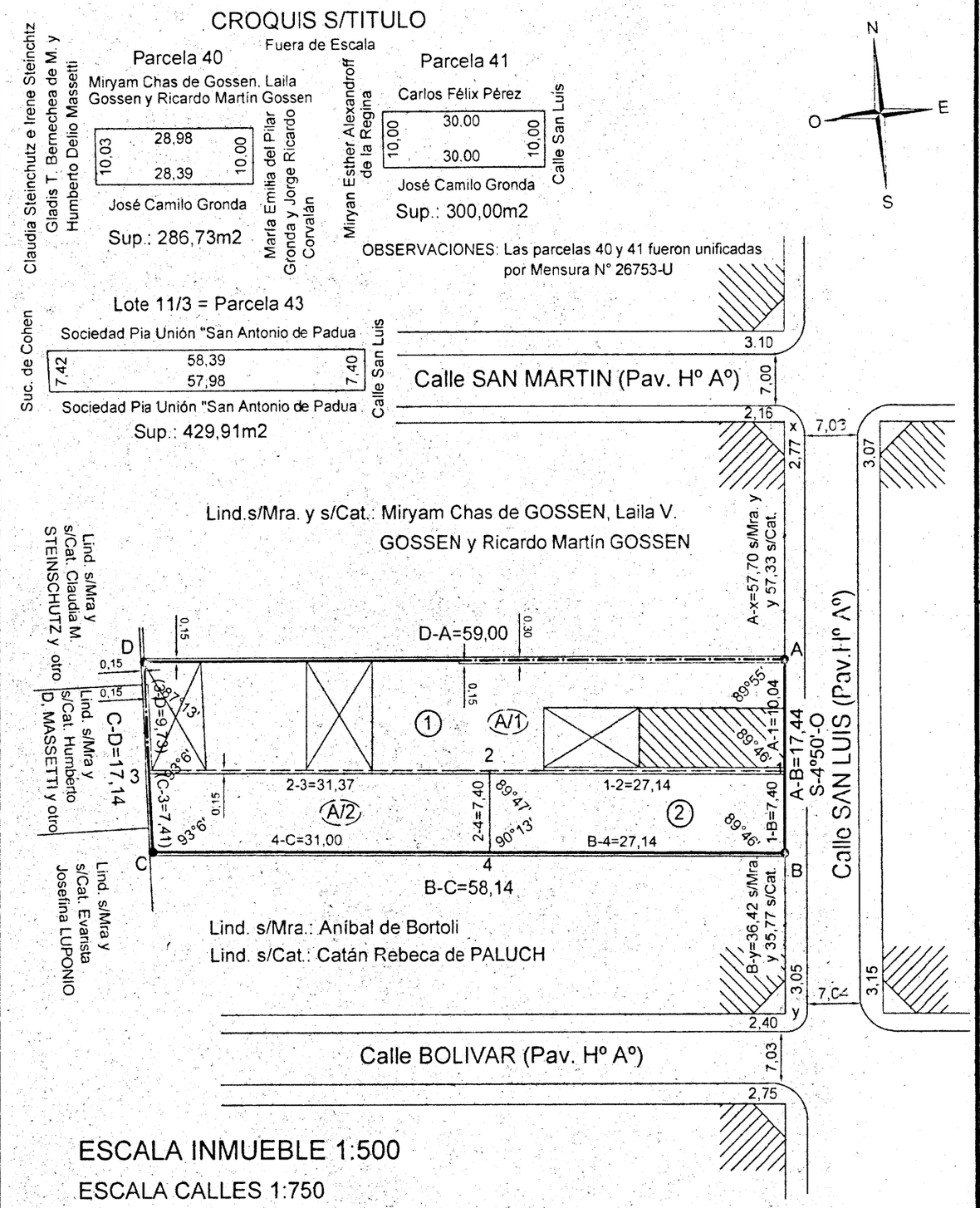

ESCALA INMUEBLE 1:500

ESCALA CALLES 1:750

SUPERFICIE SEGUN UNIFICACION

Sup. s/planilla = 1.012,03 m2

REDISTRIBUCION PARCELARIA

Sup. Parcela A/1 : 580,41 m2

Sup. Parcela A/2 : 230,77 m2

Sup. Parcela 1 : 811,18 m2

Sup. Parcela 2 : 200,84 m2

REFERENCIAS:

- Roblón de hierro colocado
- Linea de mensura
- Muros
- Edificación
- Pared medianera

NOTAS:

1) Todas las medidas lineales en metros.
2) Rumbo adoptado del lado A-B de la Mra. 10665-U para el lado A-B de las presentes operaciones.
3) Las presentes operaciones se superpone con la mensura 10665-U y parcialmente con la mensura 18505-U
4) Las presentes operaciones se autorizó por vía de excepción según Ordenanza 6969/2020 y Resolución N° 3285/2020
5) El presente plano de Mensura, Proyecto de Unificación y Redistribución Parcelaria fue visado por la Municipalidad de la Ciudad de Corrientes por Exte. 567-G-2.018

CROQUIS DE UBICACION

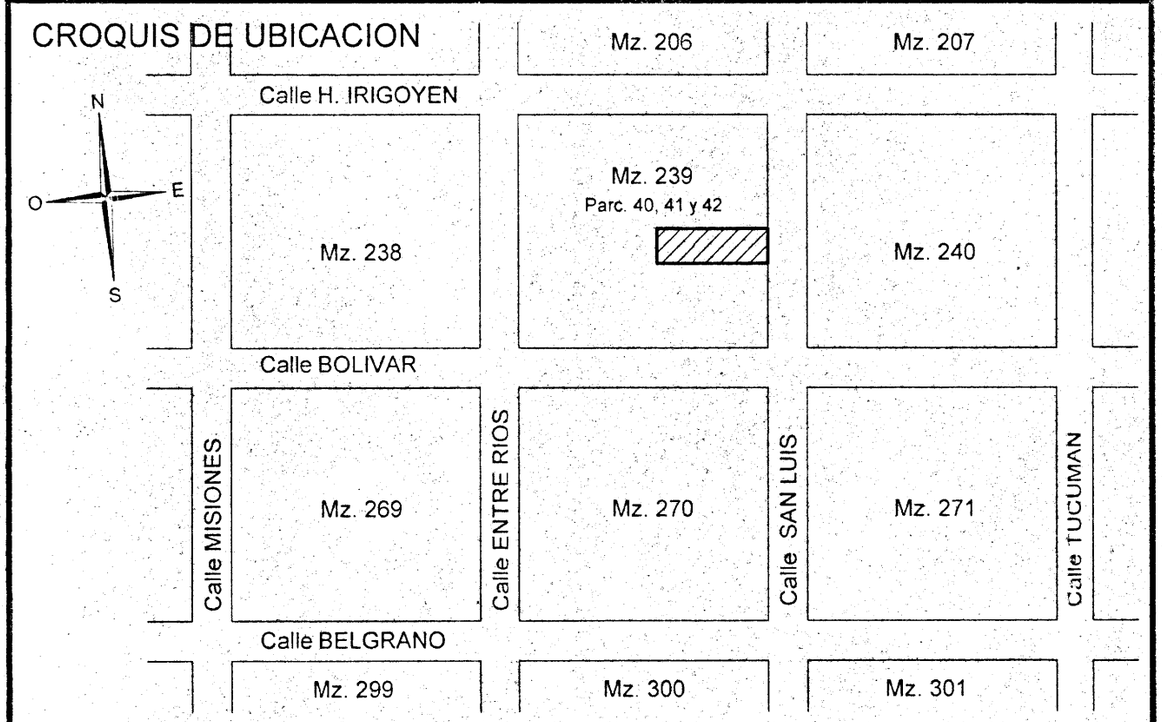

CORRIENTES, 04 de junio de 2.021.-

RAUL ROBERTO RUVEDA
Agrim. Nacional
M.C.P. 2009 - D.G.C y C. 742
Domic.: Gob. Lagraña Nº 279 - Ctes.-

MINISTERIO DE HACIENDA Y FINANZAS - DIRECCION GENERAL DE CATASTRO - CORRIENTES

MARIA EMILIA del P. GRONDA
Propietaria y P/A
D.N.I.Nº 16.357.480
Domic.: San Luis Nº 1170 - Ctes.-

MARTA H. BALCASTRO
AGRIMENSOR NACIONAL
Dección. Gral. de Catastro y Cartografía

DIRECCION GENERAL DE CATASTRO Y CARTOGRAFIA
PROVINCIA DE CORRIENTES
MENSURA REGISTRADA
CON EL Nº 29864'U
CTES. 04 DE agosto DE 2021.

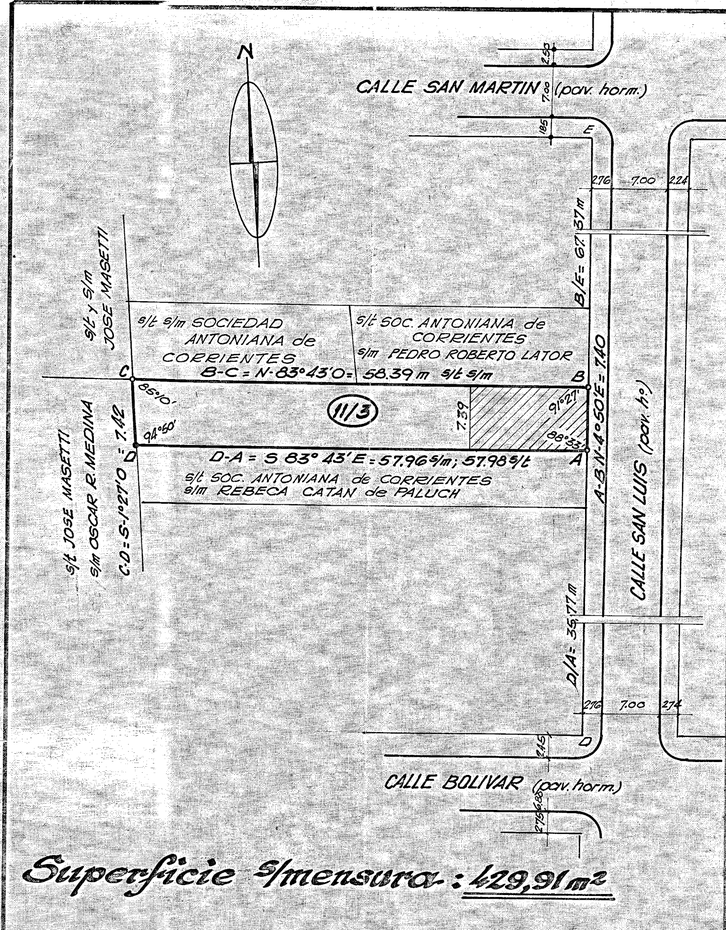

Superficie s/mensura: 429,91 m²

NOTAS:

a) El título no menciona superficie
b) Se ha tenido como antecedente el plano de Remensura y División practicada por el Agrimensor Eduardo E. Carballo que se encuentra archivado en la Direc. Gral. de Catastro bajo Dupl. 2452 "U"

ESCALA 1:500

OBJETO: REMENSURA Y DESLINDE DE LA PROPIEDAD

CARACTER: PARTICULAR

PROVINCIA DE CORRIENTES - (REP. ARGENTINA)

DEPARTAMENTO: CAPITAL

LUGAR: MUNICIPIO DE CORRIENTES

DUP. DE MENSURA: 3140 - U

NOMEN. CATASTRAL

PROPIETARIA: Tomasa Ramona SAMUDIO de PATIÑO

UBICACION: MANZANA Nº 239 - LOTE Nº 11/3

DOMINIO: Reg. Prop. Tomo 6 - Folio 1.346 - Nº 1210 - Fecha 8/10/1968 -
Reg. Prop. Munic. Folio 1467 - Finca 1.411 - Tomo 8 - Libro 5° - Fecha 5/11/1968

ADREMA: A1 - 10.192 - 1

CROQUIS DE UBICACION

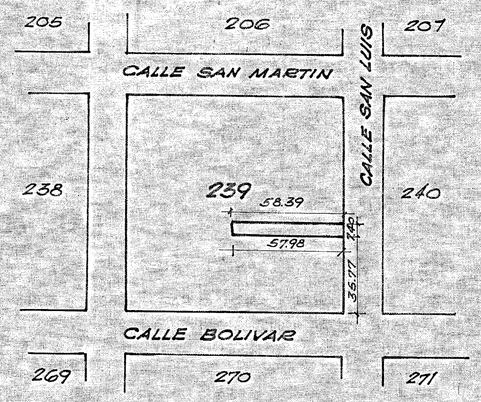

CORRIENTES, 9 DE MAYO DE 1970

Agrim. Nac. DARIO PEREZ
Cja. Prof. Nº 392
Catastro Matr. Nº 316
AV. Mdipú 787

Tomasa R. S. de Patiño
TOMASA RAMONA S. de PATIÑO
Propietaria
L.E. 6.191.982