INFORME TÉCNICO OFICIAL
ADREMA: A10169791

PROPIETARIO: GARCIA NAVARRETE, FCO. P.

UBICACIÓN: DEPARTAMENTO: CAPITAL - LOCALIDAD: CAPITAL - SECCIÓN: - - CALLE: SAN LUIS - NRO: 1063 - MANZANA: 0207 - LOTE: 13B

GEOMETRÍA DEL SUELO

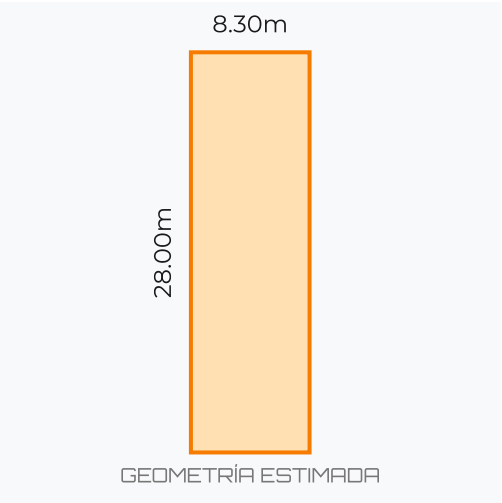

DISTRITO
CN

SUPERFICIE TOTAL
232.36 m²

FRENTE LOTE
8.3 m

INCIDENCIA ESTIMADA
ALTA
MULTIPLICADOR DE SUELO

OCUPACIÓN (F.O.S.)

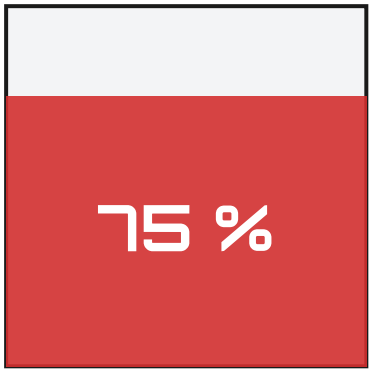

FOS: 0.75
Representación de ocupación
en Planta Baja

ENVOLVENTE VERTICAL NORMATIVA

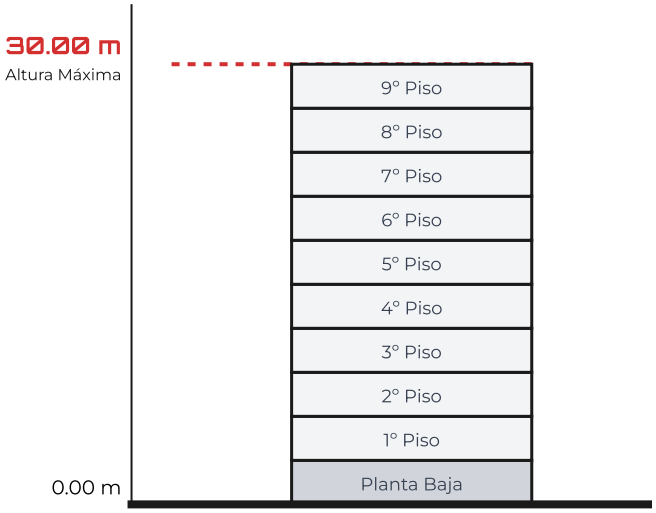

Potencial: PB + 9 Pisos

ANÁLISIS DE INTELIGENCIA ARTIFICIAL

El análisis urbanístico de la partida A10169791 revela un potencial significativo para el desarrollo sostenible. La superficie de 232.36 m² y el FOS de 0.75 sugieren una edificabilidad de 174 m², ideal para proyectos que integren áreas comerciales y residenciales. La altura máxima de 30 m permite aprovechar la verticalidad, enriqueciendo el paisaje urbano. La ubicación estratégica del distrito CN Sup. Parcela: 232.36 m² Frente: 8.3 m favorece la conectividad, mientras que el frente de 8.3 m facilita un acceso fluido. Se recomienda fomentar el diseño innovador que respete el entorno y promueva la cohesión social.

POTENCIAL CONSTRUCTIVO

PB + 9 PISOS ALTOS (30m)

TABLA DE VALUACIÓN PRELIMINAR

INDICADOR	VALOR ESTIMADO
Sup. Vendible Estimada (bruta)	**1264.00 m²**
Costo Construcción	U$S 1050 / m²
Ticket Venta Promedio	U$S 2100 / m²
RENTABILIDAD BRUTA	**ALTO POTENCIAL**

CONCLUSIÓN FINAL

La altura máxima de 30m, con una estimación conservadora de 3m por nivel, permite la construcción de un edificio de 10 plantas (Planta Baja + 9 pisos tipo). Asumiendo una ocupación similar en las plantas superiores, la superficie bruta total estimada ascendería a 1580.00 m². Aplicando un factor de eficiencia del 80% para obtener la superficie vendible, se proyectan aproximadamente 1264.00 m² de superficie comercializable. Un costo de construcción promedio de U$S 1050/m² (valor extraído de la planilla "TABLA DE VALUACIÓN PRELIMINAR") y venta de U$S 2100/m² (valor extraído de la planilla "TABLA DE VALUACIÓN PRELIMINAR"), el costo total ascendería a U$S 1.659.000 y los ingresos por venta a U$S 2.654.400. Esto arroja un margen bruto significativo de U$S 995.400.

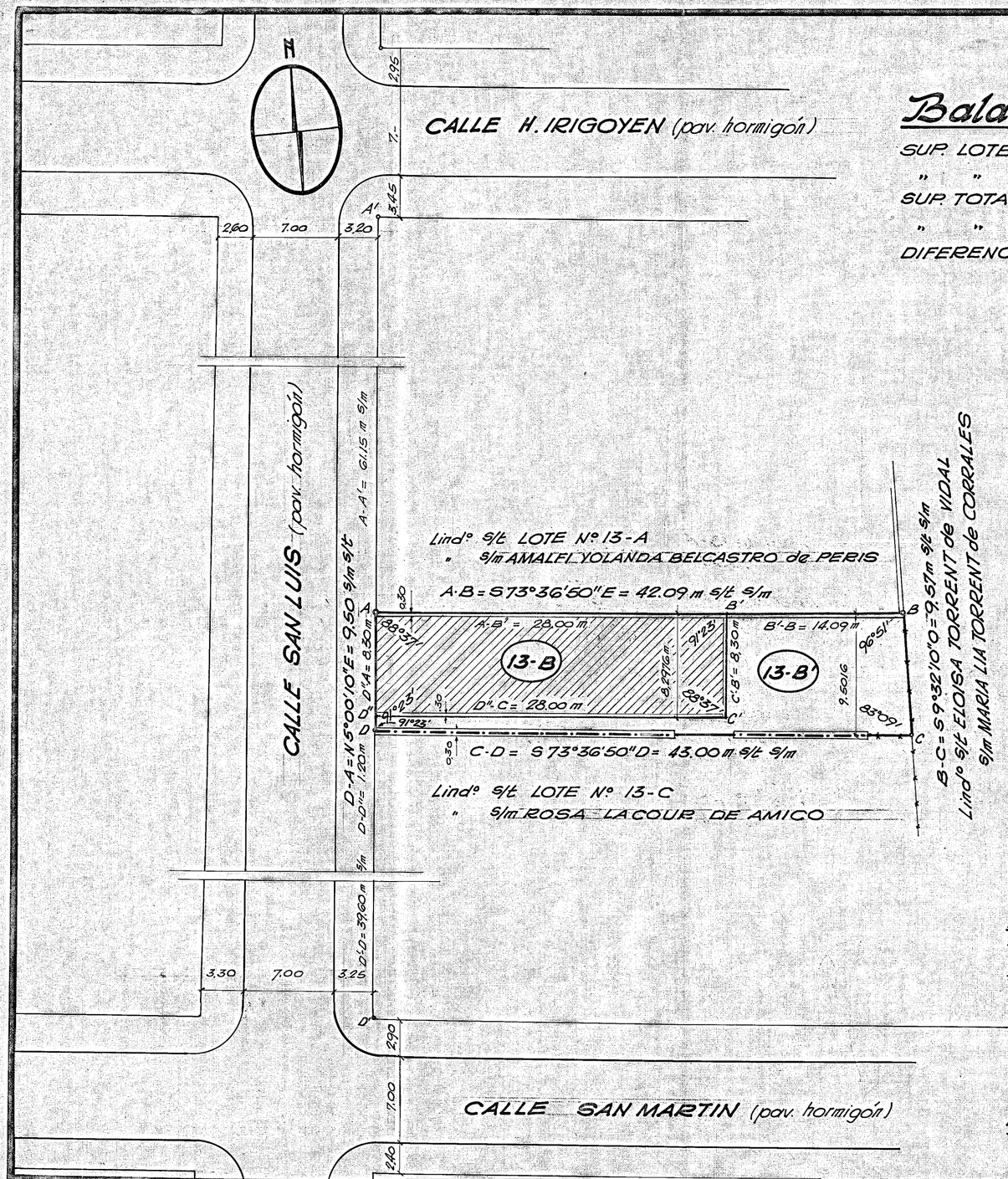

Balance de Superficies

SUP. LOTE 13-B	=	232,3328	m²
" " 13-B'	=	171,7820	"
SUP. TOTAL s/m	=	404,1148	m²
" " s/t	=	404,1973	"
DIFERENCIA EN (-)	=	0,0825	m²

NOTAS
* Los angulos no consignados son suplementarios
* Rumbo adoptado del Dup. N° 2825 "U"

OBJETO: REMENSURA Y DIVISION DEL LOTE 13 DEL DUPLICADO 2232 "U"
CARACTER: PARTICULAR
PROVINCIA DE CORRIENTES - REP. ARGENTINA
DEPARTAMENTO: CAPITAL
LUGAR: MUNICIPIO DE CORRIENTES

DUP. DE MENSURA: 3356-U
NOMENC. CATASTRAL:

PROP. DE Carlos Lorenzo GONZALEZ

UBICACION: MANZANA N° 207 - LOTE N° 13-B
Calle: San Luis entre H. Irigoyen y S. Martín

DOMINIO:
REG. DE LA PROP. DPTO. CAPITAL
N° 1033 - F° 1157 - T° 5° (10-IX-68)
REG. DE LA PROP. MUNICIPAL
F° 1281 - Finca 1227 - T 7° - L 4° - (26-IX-68)
ADREMA A1 - 16.979-1 (20-IX-68)

12

CROQUIS DE UBICACION

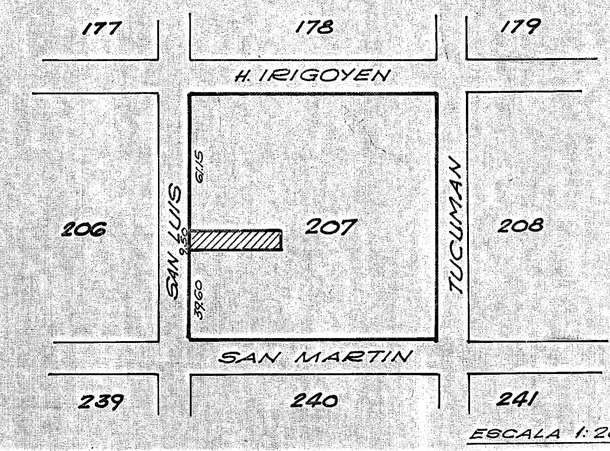

CORRIENTES, 3 DE NOVIEMBRE DE 1970

DARIO PEREZ	DANIEL QUIROZ	CARLOS LORENZO GONZALEZ
Agrimensor Nacional	Agrimensor Nacional	Propietario
C.P.N° 392 - Matr. N° 316	C.P.N° 350 - Matr. 297	M.I. N° 5.627.267
Av. Maipú 787	Rep. del Líbano 296	